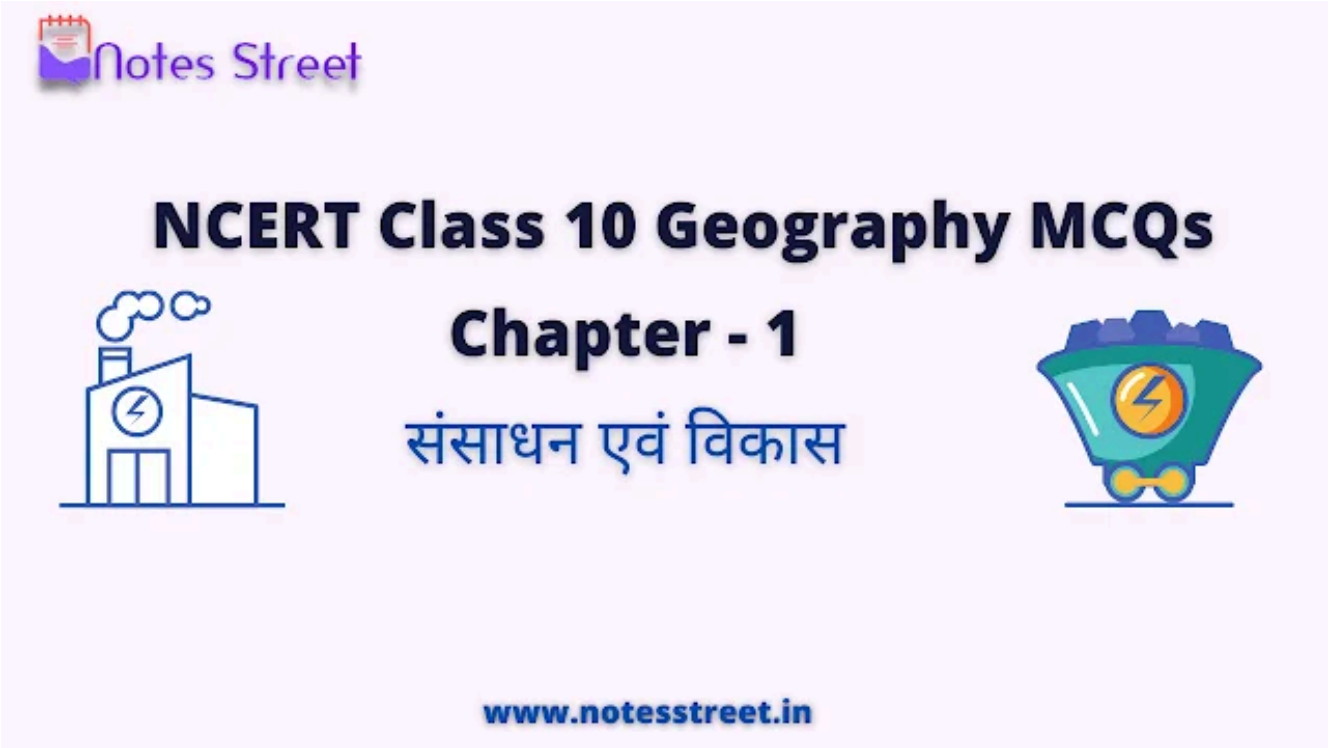


NCERT Class 10 Geography MCQs Chapter - 1 संसाधन एवं विकास

NCERT Class 10 Geography MCQs

---

**Old Coin Buyer**

NCERT Class 10 Geography MCQs Chapter – 1 संसाधन एवं विकास

1. किसने कहा-“संसाधन होते नहीं बनते हैं।”
(A) जिम्मरमैन
(B) महात्मा गाँधी
(C) संदीप पांडेय
(D) इनमें से कोई नहीं
Ans:-(A)

2. निम्नलिखित में से कौन-सा संसाधन प्राकृतिकसंसाधन है?
(A) भूमि
(B) भवन
(C) मानव की योग्यता
(D) इनमें से कोई नहीं

Ans:-(A)

3. ज्वारीय एवं तरंग ऊर्जा उत्पादन हेतु भारत केअधिक अनुकूल परिस्थितियाँ कहाँ पाई जाती है?
(A) मन्नार की खाड़ी में
(B) खम्भात की खाड़ी में
(C) गंगा नदी में
(D) कोसी नदी में
Ans:-(B)

4. कौन-सा ऊर्जा स्रोत अनवीकरणीय है?
(A) जल
(B) सौर
(C) कोयला
(D) पवन
Ans:-(C)

5. ज्वारीय ऊर्जा किस प्रकार का संसाधन है?
(A) नवीकरणीय
(B) अजैव
(C) मानवकृत
(D) जैव
Ans:-(A)

6. कौन-सा ऊर्जा स्रोत नवीकरणीय है?
(A) प्राकृतिक गैस
(B) जल
(C) कोयला
(D) पेट्रोलियम
Ans:-(B)

7. इनमें किस प्राकृतिक संसाधन का भंडार सीमित है?
(A) खनिज तेल का
(B) सौर ऊर्जा का
(C) हवा का
(D) पानी का
Ans:-(A)

8. भारत में विद्युत की सबसे अधिक खपत किसमें होती है?
(A) घरेलू कामों में
(B) व्यापारिक कामों में

(C) उद्योगों में
(D) कृषि कामों में
Ans:-(C)

9. समुद्री क्षेत्र में राजनैतिक सीमा के कितनी किलोमीटर क्षेत्र तक राष्ट्रीय संपदा निहित है?
(A) 10.2 किमी०
(B) 15.5 किमी०
(C) 12.2 किमी०
(D) 19.2 किमी०
Ans:-(D)

10. तट रेखा से कितने किमी० क्षेत्र सीमा अपवर्जकआर्थिक क्षेत्र कहलाती है?
(A) 100 किमी०
(B) 200 किमी०
(C) 150 किमी०
(D) 250 किमी०
Ans:-(B)

11. "हमारे पास पेट भरने के लिए बहुत कुछ है, लेकिन पेटी भरने के लिए नहीं"। यह कथनकिसका है?
(A) नेहरू जी का
(B) मेधा पाटेकर का
(C) गाँधी जी का
(D) सुन्दर लाल बहुगुणा का
Ans:-(C)

12. संसाधनों के संरक्षण हेतु सर्वप्रथम किसने वकालतकी थी?
(A) नेहरू जी ने
(B) क्लव ऑफ रोम ने
(C) संयुक्त राष्ट्र ने
(D) जापान ने
Ans:-(B)

13. प्राकृतिक संसाधनों के संरक्षण हेतु अफ्रीकी कनवेंशन किस वर्ष हुआ था?
(A) 1960
(B) 1968
(C) 1972
(D) 1980
Ans:-(B)

14. विश्व पर्यावरण दिवस किस तिथि को मनाया जाता है?

(A) 2 जून
(B) 5 जून
(C) 4 जून
(D) 7 जून
Ans:-(B)

15. प्रथम पृथ्वी सम्मेलन 1992 किस देश में आयोजित किया गया?
(A) ब्राजील
(B) भारत
(C) जापान
(D) दक्षिण अफ्रीका
Ans:-(A)

16. द्वितीय पृथ्वी सम्मेलन कहाँ हुआ था?
(A) न्यूयार्क.
(B) पेरिस
(C) मास्को
(D) इनमें से कोई नहीं
Ans:-(A)

17. क्योटो सम्मेलन किस देश में आयोजित की गईथी?
(A) फ्रांस
(B) म्यानमार
(C) जापान
(D) इंडोनेशिया
Ans:-(C)

18. भारत में पहाड़ों से भरी भूमि कितना प्रतिशत है?
(A) 10
(B) 27
(C) 30
(D) 48
Ans:-(C)

19. मृदा निर्माण में निम्न प्रक्रियाएँ शामिल होती है-
(A) अपक्षय
(B) अपरदन
(C) दोनों
(D) इनमें से कोई नहीं
Ans:-(C)

20. प्रायद्धीपीय भारत की नदी घाटियों में कौन-सी मिट्टी मिलती है?
(A) काली मिट्टी
(B) लाल मिट्टी
(C) रेतीली मिट्टी
(D) जलोढ़ मिट्टी
Ans:-(D)

21. भारत में सबसे अधिक विस्तार किस मिट्टी काहै?
(A) जलोढ़ मिट्टी
(B) काली मिट्टी
(C) लेटेराइट मिट्टी
(D) वनीय मिट्टी
Ans:-(A)

22. पुरानी जलोढ़ मिट्टी को क्या कहा जाता है?
(A) बॉगर
(B) खादर
(C) यॉवर
(D) रेगड़
Ans:-(A)

23. जलोढ़ मिट्टी में कौन-सा तत्त्व प्रचुर मात्रा में पाया जाता है?
(A) पोटाश
(B) फास्फोरस
(C) नाइट्रोजन
(D) जीवांम
Ans:-(A)

24. भारत की सबसे उपजाऊ मिट्टी है-
(A) लेटराइट मिट्टी
(B) जलोढ़ मिट्टी
(C) लाल मिट्टी
(D) पर्वतीय मिट्टी
Ans:-(B)

25. काली मिट्टी उपयुक्त है-
(A) कपास के लिए
(B) लीची के लिए
(C) गेहूँ के लिए

(D) बाजरा के लिए
Ans:-(A)

26. इनमें से किस राज्य में काली मृदा पाई जाती है ?
(A) जम्मू और काश्मीर
(B) झारखंड
(C) राजस्थान
(D) महाराष्ट्र
Ans:-(D)

27. काली मिट्टी का दूसरा नाम क्या है ?
(A) बलुई मृद
(B) रेगुर मृदा
(C) लाल मृदा
(D) पर्वतीय मृदा
Ans:-(B)

28. लेटेराइट मृदा का रंग होता है ?
(A) पीला
(B) लाल
(C) काला
(D) भूरा
Ans:-(B)

29. मरुस्थलीय मृदा का विस्तार निम्न में से कहाँ है?
(A) उत्तर प्रदेश
(B) राजस्थान
(C) कर्नाटक
(D) महाराष्ट्र
Ans:-(B)

30. मरुस्थली मृदा का विस्तार निम्न में से कहाँ है?
(A) उत्तरप्रदेश
(B) राजस्थान
(C) कर्नाटक
(D) पंजाब
Ans:-(B)

31. भारत में चारागाह के अंतर्गत कितनी भूमि है?
(A) 4%

(B) 12%
(C) 19%
(D) 15%
Ans:-(A)

32. पंजाब में भूमि निम्नीकरण का मुख्य कारण है
(A) वनोन्मूलन
(B) गहन खेती
(C) अति पशुचारण
(D) अधिक सिंचाई
Ans:-(D)

33. इनमें कौन उपाय भूमि ह्रास के संरक्षण मेंउपयुक्त हो सकता है ?
(A) भूमि को जलमग्न बनाये रखना
(B) बाढ़ नियंत्रण
(C) जनसंख्या वृद्धि की दर में तेजी लाना
(D) इनमें से कोई नहीं
Ans:-(B)

34. भारत में भूदान के लिए रक्तहीन क्रांति कीशुरुआत किसने की थी ?
(A) विनोवा भावे
(B) रामचंद्र रेड्डी
(C) सुभाषचन्द्र बोस
(D) जयप्रकाश नारायण
Ans:-(A)

35. मेढ़क को प्रजनन प्रक्रिया को बाधित करने वाला रसायन कौन-सा है?
(A) बेंजीन
(B) यूरिया
(C) एंड्रिन
(D) फॉस्फोरस
Ans:-(C)

36. जल किस प्रकार का संसाधन है ?
(A) चक्रीय
(B) जैव
(C) अजैव
(D) अनवीकरणीय
Ans:-(A)

37. पृथ्वी के किस गोलार्द्ध को जल गोलार्द्ध कहाजाता है?
(A) उत्तरी गोलार्द्ध को
(B) दक्षिणी गोलार्द्ध को
(C) दोनों ही गोलार्द्ध को
(D) इनमें से कोई नहीं
Ans:-(B)

38. कुल जल का कितना प्रतिशत भाग महासागरोंमें निहित है?
(A) 9.5%
(B) 95.5%
(C) 96%
(D) 96.5%
Ans:-(D)

39. विश्व के कुल जल आयतन का कितना प्रतिशत मृदु जल है?
(A) 2%
(B) 2.5%
(C) 3%
(D)3.5%
Ans:-(B)

40. हिमालय क्षेत्र में प्रवाहित होने वाली नदियाँ निम्नलिखित में से किस प्रकार की प्रवाह प्रणाली प्रस्तुत करती है?
(A) पूर्वारोपित
(B) पूर्ववर्ती
(C) वलयाकार
(D) आयताकार
Ans:-(B)

41. हिमालय के अपवाह तंत्र में जो नदी तंत्र सम्मिलित नहीं है, वह है?
(A) गंगा नदी
(B) ब्रह्मपुत्र नदी
(C) सिन्धु नदी
(D) महानदी
Ans:-(D)

42. निम्न में से कौन-सी नदी भारत-नेपाल के मध्य सीमा बनाती है?
(A) काली
(B) गण्डक
(C) कोसी

(D) तिस्ता
Ans:-(A)

43. प्राणियों के शरीर में कितना प्रतिशत जल कीमात्रा निहित होती है?
(A) 55%
(B) 60%
(C) 65%
(D) 70%
Ans:-(C)

44. भारत में जल का सबसे अधिक उपयोग किया जाता है?
(A) सिंचाई में
(B) उद्योग में
(C) घरेलु उपयोग में
(D) व्यापार में
Ans:-(A)

45. भारत में कितने प्रतिशत जल का उपयोग घरेलू तथा नगरीय आपूर्ति में किया जाता है?
(A) 70%
(B) 11%
(C) 19%
(D) इनमें से कोई नहीं
Ans:-(B)

46. भारत की सबसे बड़ी कृत्रिम झील कौन है?
(A) चिलका झील
(B) लोनार झील
(C) गाँधी सागर झील
(D) गोविंद वल्लभ पंत सांगर
Ans:-(D)

47. नागार्जुन सागर परियोजना किस नदी पर अवस्थित है?
(A) नर्मदा नदी
(B) गोदावरी नदी
(C) कृष्णा नदी
(D) ताप्ती नदी
Ans:-(C)

48. इंदिरा गाँधी नहर परियोजना किस राज्य की महत्त्वाकांक्षी परियोजना है?
(A) मध्य प्रदेश

(B) राजस्थान
(C) महाराष्ट्र
(D) आंध्रप्रदेश
Ans:-(B)

49. निम्न में राजस्थान की सबसे महत्त्वपूर्ण योजनाकौन-सी है?
(A) चम्बल परियोजना
(B) नागार्जुन सागर परियोजना
(C) भाखड़ा नंगल परियोजना
(D) इंदिरा गाँधी नहर परियोजना
Ans:-(D)

50. भारत की सबसे लंबी नहर कौन है?
(A) सोन नहर
(B) भाखड़ा-नांगल नहर
(C) गंडक नहर
(D) इंदिरा गाँधी नहर
Ans:-(D)

51. बिहार की पहली नदी घाटी परियोजना कौन है?
(A) गण्डक नदी घाटी परियोजना
(B) कोसी नदी घाटी परियोजना
(C) बागमती परियोजना
(D) सोन नदी घाटी परियोजना
Ans:-(D)

52. इन्द्रपुरी जलाशय परियोजना किस राज्य में है?
(A) बिहार
(B) छत्तीसगढ़
(C) केरल
(D) असम
Ans:-(A)

53. “वाण सागर” नामक जलाशय का निर्माण किस नदी पर किया गया है?
(A) महानदी
(B) सोन नदी
(C) कोसी नदी
(D) सतलज नदी
Ans:-(B)

54. प्रतिव्यक्ति प्रतिवर्ष जल उपलब्धता के आधारपर विश्व में भारत का कौन-सा स्थान है?
(A) 100वाँ
(B) 113वाँ
(C) 123वाँ
(D) 133वाँ
Ans:-(D)

55. इनमें कौन मछलियों के अस्तित्व को खतरे में डाल सकता है?
(A) वर्षा जल
(B) सागर जल
(C) दूषित जल
(D) मानव निर्मित बाँध
Ans:-(C)

56. सर्वाधिक वर्षा होती है-
(A) पूर्णिया में
(B) चेरापूँजी में
(C) कोच्चि में
(D) मावसिनराम मे
Ans:-(D)

57. वर्षा जल संग्रहण के ढाँचों को हर घर में बनाना किस राज्य में अनिवार्य है?
(A) बिहार में
(B) उत्तरप्रदेश में
(C) उड़ीसा में
(D) तमिलनाडु में
Ans:-(D)

58. भारत सरकार ने कब राजीव गांधी राष्ट्रीयपेयजल मिशन चालू किया?
(A) 1956
(B) 1966
(C) 1976
(D) 1986
Ans:-(D)

69. एक एन०जी०ओ० की वानिकी रिपोर्ट केअनुसार1948 में विश्व में कितने हेक्टेयर भूमि पर वन का विस्तार था?
(A) 6 अरब हेक्टेयर
(B) 4 अरब हेक्टेयर
(C) 8 अरब हेक्टेयर

(D) 5 अरब हेक्टेयर
Ans:-(B)

60. भारत में 2011 के अनुसार कितने प्रतिशत भौगोलिक क्षेत्र में वन का विस्तार है?
(A) 25
(B) 19.27
(C) 21.23
(D) 20.60
Ans:-(C)

61. भारत की राष्ट्रीय वन नीति के अनुसार देश केकितने प्रतिशत भू-भाग पर वन रहना चाहिए।
(A) 20%
(B) 22.5%
(C) 33.3%
(D) 40%
Ans:-(C)

62. सुंदरवन है-
(A) कर्नाटक में
(B) पश्चिम बंगाल में
(C) केरल में
(D) महाराष्ट्र में
Ans:-(B)

63. पूर्वोतर राज्यों के 188 आदिवासी जिलों में देश के कुल क्षेत्र का कितना प्रतिशत वन है?
(A) 75%
(B) 80.05%
(C) 90.03%
(D) 60.11%
Ans:-(D)

64. वन संरक्षण एवं प्रबंधन की दृष्टि से वनों कोवर्गीकृत किया गया है-
(A) 4 वर्गों में
(B) 3 वर्गों में
(C) 5 वर्गों में
(D) इनमें से कोई नहीं
Ans:-(B)

65. भारत में सर्वाधिक महत्त्वपूर्ण व्यावसायिक वन है।
(A) ऊष्ण कटिबंधीय सदाबहार वन

(B) ऊष्ण कटिबंधीय पतझड़ वन
(C) कोणधारी वन
(D) ऊष्ण कटिबंधीय अर्द्ध-सदाबहार वन
Ans:-(B)

66. चंदन किस प्रकार के वन में पाये जाते हैं?
(A) सदावहार वन
(B) शुष्क वन
(C) पतझड़ बन
(D) पर्वतीय वन
Ans:-(C)

67. देवदार किस प्रकार के वन के वृक्ष है?
(A) पर्वतीय वन
(B) सदावहार वन
(C) पतझड़ वन
(D) शुष्क वन
Ans:-(A)

68. इनमें कौन वन और वन्य प्राणियों में विनाश का कारण नहीं है?
(A) कृषि क्षेत्रों में अत्यधिक वृद्धि
(B) बड़े पैमाने पर विकास कार्यों का होना
(C) व्यापार में वृद्धि
(D) पशुचारण एवं लकड़ी कटाई
Ans:-(C)

69. कुनैन किस रोग की दवा है?
(A) दमा
(B) कैंसर
(C) मलेरिया
(D) पेचिश
Ans:-(C)

70. निम्न में कौन हमारे देश से प्राय: लुप्त हो चुका है?
(A) चीता
(B) हनुमान
(C) गैंडा
(D) तेंदुआ
Ans:-(A)

71. किस वर्ग की विलुप्त प्रजातियों की संख्या सबसे अधिक है?
(A) वनस्पति
(B) पत्ती
(C) मछलियाँ
(D) सरीसृप
Ans:-(A)

72. भारत की संकटग्रस्त पादप प्रजातियों की एक सूची किस नाम से प्रकाशित की गई है?
(A) रेड डाटा बुक
(B) ग्रीन डाटा बुक
(C) गुलाबी डाटा बुक
(D) ब्लू डाटा बुक
Ans:-(A)

73. संविधान की धारा 21 का संबंध है-
(A) वन्य जीवों तथा प्राकृतिक संसाधनों के संरक्षण
(B) मृदा संरक्षण
(C) जल संसाधन संरक्षण
(D) खनिज संपदा संरक्षण
Ans:-(A)

74. भारतीय संविधान की धारा 51ए (जी) का संबंध किससे है?
(A) जल संसाधन संरक्षण
(B) मृदा संसाधन संरक्षण
(C) वन्य जीव और वनस्पतियों का संरक्षण
(D) प्राकृतिक संसाधन का संरक्षण
Ans:-(C)

75. घाना पक्षी बिहार किस राज्य में अवस्थित है?
(A) बिहार
(B) झारखंड
(C) गुजरात
(D) राजस्थान
Ans:-(D)

76. कार्बेट राष्ट्रीय उद्यान भारत के किस राज्य मेंअवस्थित है?
(A) असम
(B) उड़ीसा
(C) उत्तर प्रदेश
(D) उत्तराखंड

Ans:-(D)

77. मानस तथा काजीरंगा अभयारण्य किस राज्य मेंस्थित है?
(A) असम
(B) बिहार
(C) उत्तराखंड
(D) पश्चिम बंगाल
Ans:-(A)

78. गिर राष्ट्रीय उद्यान किस राज्य में अवस्थित है?
(A) असम
(B) उड़ीसा
(C) गुजरात
(D) राजस्थान
Ans:-(C)

79. सुन्दरवन टाइगर रिजर्व कहाँ है?
(A) पश्चिम बंगाल
(B) ओडिशा
(C) उत्तराखंड
(D) केरल
Ans:-(A)

80. इनमें कौन शाकाहारी नहीं है?
(A) गैंडा
(B) बारहसिंगा
(C) हिरण
(D) भेड़िया
Ans:-(D)

81. भारत में घड़ियाल प्रजनन केन्द्र कहाँ स्थापितकिया गया है?
(A) मुरैना (मध्यप्रदेश)
(B) सुन्दरवन (पं० बंगाल)
(C) नमदफा (अरुणाचल प्रदेश)
(D) कार्बेट (उत्तराखंड)
Ans:-(A)

82. भारत में सफेद बाघ के लिए प्रजनन-केंद्र किसराज्य में स्थापित किया गया है?
(A) महाराष्ट्र में
(B) गुजरात में

(C) उड़ीसा में
(D) आंध्रप्रदेश में
Ans:-(C)

83. भारत में बाज परियोजना की शुरुआत कब हुई थी?
(A) 1970
(B) 1972
(C) 1973
(D) 1975
Ans:-(C)

84. "चिपको आंदोलन" कार्यक्रम किसके द्वाराचलाया गया था?
(A) मेधा पाटेकर
(B) सुन्दरलाल बहुगुणा
(C) संदीप पांडेय
(D) महात्मा गाँधी
Ans:-(B)

85. संसार का सबसे कीमती संसाधन कौन है?
(A) पशु
(B) वन
(C) खनिज
(D) नदियाँ
Ans:-(C)

86. किस प्रकार की चट्टानों में खनिजों का जमाव परतों में मिलता है?
(A) आग्नेय
(B) अवसादी
(C) रूपांतरित
(D) इनमें से कोई नहीं
Ans:-(B)

87. निम्नलिखित में कौन लौह अयस्क का एक प्रकारहै?
(A) लिगनाइट
(B) हेमाटाइट
(C) विटुमिनस
(D) इनमें से सभी
Ans:-(B)

88. इनमें से कौन लौह अयस्क का एक प्रकार नहीं है?

(A) एंथ्रासाइट
(B) हेमाटाइट
(C) मैग्नेटाइट
(D) लाइमोनाइट
Ans:-(A)

89. निम्नांकित में से किस खनिज में भारत सुसंपन्नहै?
(A) सोना
(B) चाँदी
(C) ताँबा
(D) लोहा
Ans:-(D)

90. कौन भारत का सबसे बड़ा लौह उत्पादक राज्यहै?
(A) कर्नाटक
(B) गोवा
(C) उड़ीसा
(D) झारखंड
Ans:-(A)

91. बाबाबूदन की पहाड़ी किस राज्य में स्थित है?
(A) झारखंड
(B) उड़ीसा
(C) छत्तीसगढ़
(D) कर्नाटक
Ans:-(D)

92. नोआमुंडी किस राज्य में स्थित है?
(A) झारखंड
(B) उड़ीसा
(C) मध्यप्रदेश
(D) आंध्रप्रदेश
Ans:-(A)

93. भारत का लोहा किस देश को निर्यात किया जाता है?
(A) रूस
(B) जापान
(C) श्रीलंका
(D) चीन
Ans:-(B)

94. इनमें कौन लोहे का निर्यात नहीं करता है?
(A) मुंबई
(B) कोलकाता
(C) पारादीप
(D) विशाखापट्नम
Ans:-(A)

95.मैंगनीज उत्पादन में भारत का विश्व में क्या स्थान है?
(A) प्रथम
(B) द्वितीय
(C) तृतीय
(D) चतुर्थ
Ans:-(C)

96. मैंगनीज का उपयोग किया जाता है?
(A) बैटरी निर्माण में
(B) फोटोग्राफी उद्योग में
(C) माचिस उद्योग में
(D) इनमें सभी
Ans:-(D)

97. निम्न में से कौन-सा राज्य मैंगनीज का सबसे बड़ा उत्पादक राज्य है?
(A) महाराष्ट्र
(B) उड़ीसा
(C) गुजरात
(D) मध्यप्रदेश
Ans:-(B)

98. इनमें कौन मैंगनीज का महत्त्वपूर्ण उत्पादक नहीं है?
(A) उड़ीसा
(B) कर्नाटक
(C) तमिलनाडु
(D) महाराष्ट्र
Ans:-(C)

99. भारत में बॉक्साइट का सबसे बड़ा उत्पादक राज्य
(A) केरल
(B) उड़ीसा
(C) मध्यप्रदेश

(D) बिहार
Ans:-(B)

100. झारखंड का घाटशिला किस खनिज उत्पादनके लिए प्रसिद्ध है?
(A) ताँबा
(B) बॉक्साइट
(C) अभ्रक
(D) लौह अयस्क
Ans:-(A)

102. कोयला है
(A) अनवीकरणीय संसाधन
(B) नवीकरणीय संसाधन
(C) जैव संसाधन
(D) इनमें से कोई नहीं
Ans:-(A)

103. निम्नलिखित में से कौन-सा परंपरागत ऊर्जा का स्रोत है?
(A) वायो गैस
(B) ज्वारीय गैस
(C) सौर ऊर्जा
(D) कोयला
Ans:-(D)

104. ऊर्जा का गैर परम्परागत स्रोत क्या है?
(A) प्राकृतिक गैस
(B) सूर्यकिरण
(C) कोयला
(D) जल
Ans:-(B)

105. इनमें से ऊर्जा का गैर-पारम्पारिक स्रोत कौन है?
(A) ज्वारीय ऊर्जा
(B) पेट्रोलियम
(C) कोयला
(D) प्राकृतिक गैस
Ans:-(A)

106. भारत में ऊर्जा का प्रमुख स्रोत कौन-सा है?
(A) कोयला

(B) पेट्रोलियम
(C) प्राकृतिक गैस
(D) जल विद्युत
Ans:-(A)

107. गौंडवाना युग की चट्टानों में भारत का कितनाप्रतिशत कोयला मिलता है?
(A) 80%
(B) 90%
(C) 94%
(A) 98%
Ans:-(D)

108. कालाकोट कोयला क्षेत्र किस राज्य में स्थित है?
(A) अरुणाचल प्रदेश
(B) झारखंड
(C) मध्यप्रदेश
(D) जम्मू काश्मीर
Ans:-(D)

109. किस राज्य में खनिज तेल का विशाल भंडार स्थित है?
(A) असम
(B) राजस्थान
(C) बिहार
(D) तमिलनाडु
Ans:-(A)

110. पेट्रोलियम किन चट्टानों में मिलता है?
(A) आग्नेय
(B) परतदार
(C) रूपांतरित
(D) प्रत्ये
Ans:-(B)

111. डिगबोई तेल क्षेत्र कहाँ स्थित है?
(A) गुजरात में
(B) मेघालय में
(C) असम में
(D) महाराष्ट्र में
Ans:-(C)

112. अंकलेश्वर में किस शक्ति के साधन की प्रचुरताहै?
(A) कोयला
(B) जलशक्ति
(C) अणुशक्ति
(D) खनिज तेल
Ans:-(D)

113. भारत में खनिज तेल का वार्षिक उत्पादन कितना है?
(A) 72 लाख टन
(B) 7 रोड़ टन
(C) 3 करोड़ टन
(D) 9 करोड़ टन
Ans:-(C)

114. इनमें कहाँ प्राकृतिक गैस के भंडार मिले हैं?
(A) छत्तीसगढ़
(B) कर्नाटक
(C) त्रिपुरा
(D) मध्यप्रदेश
Ans:-(C)

115. भारत में सर्वप्रथम जल विद्युत गृह की स्थापना कहाँ की गई?
(A) कर्नाटक
(B) तमिलनाडु
(C) झारखंड
(D) गुजरात
Ans:-(A)

116. भाखड़ा नांगल परियोजना किस नदी पर अवस्थित है?
(A) नर्मदा नदी
(B) झेलम नदी
(C) सतलज नदी
(D) व्यास नदी
Ans:-(C)

117. निम्नलिखित बहुउद्देशीय परियोजना में से कौन-सी परियोजना झारखंड राज्य क परियोजना है?
(A) भाखड़ा नांगल परियोजना
(B) नर्मदा घाटी परियोजना
(C) दामोदर घाटी परियोजना
(D) रिहन्द परियोजना

Ans:-(C)

118. निम्नलिखित नदियों में से किसे 'बिहार काशोक' कहा जाता है?
(B) गंडक
(A) गंगा
(C) कोसी
(D) पुनपुन
Ans:-(C)

119. किस परियोजना का मुख्य उद्देश्य बाढ़ नियंत्रण है?
(A) हीराकुंड
(B) भाखड़ा-नंगल
(C) चम्बल
(D) कोसी
Ans:-(D)

120. रिहन्द किस नदी की सहायक नदी है?
(A) सोन नदी
(B) गंडक नदी
(C) चम्बल नदी
(D) गंगा नदी
Ans:-(A)

121. रिहन्द बाँध किस राज्य में है?
(A) बिहार
(B) पंजाब
(C) उत्तरप्रदेश
(D) महाराष्ट्र
Ans:-(C)

122. हीराकुण्ड परियोजना किस नदी पर स्थित है?
(A) महानदी
(B) गोदावरी
(C) कृष्णा
(D) कावेरी
Ans:-(A)

123. हीराकुण्ड बांध है-
(A) कर्नाटक में
(B) तमिलनाडु में

(C) बिहार में
(D) ओडिशा में
Ans:-(D)

124. भारत में सबसे लंबा बाँध कौन है?
(A) भाखड़ा नांगल बाँध
(B) नागार्जुन सागर बाँध
(C) हीराकुंड बाँध
(D) टेहरी बाँध
Ans:-(C)

125. निम्नांकित में कौन खनिज करल तट पर बालू के रूप में मिलता है?
(A) यूरेनियम
(B) कोयला
(C) थोरियम
(D) सोना
Ans:-(C)

126.पंजाब में भूमि निम्नीकरण का निम्नलिखित में से मुख्य कारण क्या है ?
( A ) गहन खेती
( B ) वनोन्मूलन
( C ) अधिक सिंचाई
( D ) अति पशुचारण.
Ans-( D )

127. किस खनिज को उद्योगों की जननी माना गया है ?
( A ) सोना
( B ) ताम्बा
( C ) लोहा
( D ) मैंगनीज.
Ans-( C )

128. मेढ़क के प्रजनन को नष्ट करने वाला रसायन कौन है ?
( A ) बॅजीन
( B ) यूरिया
( C ) एड्रिन
( D ) फॉस्फोरस।
Ans-( C )

129 . मरुस्थलीय मृदा का विस्तार निम्नलिखित में से कहाँ है ?
( A ) उत्तर प्रदेश
( B ) राजस्थान

( C ) कर्नाटक
( D ) महाराष्ट्र
Ans-( B )

130. सोपानी कृषि किस राज्य में प्रचलित है ?
( A ) हरियाणा
( B ) पंजाब
( C ) बिहार का मैदानी क्षेत्र
( D ) उत्तराखंड
Ans-( D )

131 . कोयला किस प्रकार का संसाधन है ?
( A ) अनवीकरणीय
( B ) नवीकरणीय
( C ) जैव
( D ) अजेव
Ans-( A )

132. भारत में 2001 ई ० में कितने प्रतिशत भौगोलिक क्षेत्र में वन का विस्तार था ?
( A ) 25 %
( B ) 19.27 %
( C ) 20 %
( D ) 20.60 %
Ans-( B )

133 . प्राणियों के शरीर में कितना प्रतिशत जल की मात्रा निहित होती है ?
( A ) 55 %
( B ) 60 %
( C ) 65 %
( D ) 70%
Ans-( C )

134. वृहत् क्षेत्र में जल की उपस्थिति के कारण पृथ्वी को कहते हैं
( A ) उजला ग्रह
( B ) नीला ग्रह
( C ) लाल ग्रह
( D ) हरा ग्रह।
Ans-( B )

135. काली मृदा का दूसरा नाम क्या है ?
( A ) बलुई मृदा
( B ) रेगुर मृदा
( C ) लाल मृदा
( D ) पर्वतीय मृदा।

Ans-( B )

136. एफ ० ए ० ओ ० की वानिकी रिपोर्ट के अनुसार 1948 ई ० में विश्व में कितने हेक्टेयर भूमि पर वन का विस्तार था ?
( A ) 6 अरब हेक्टेयर
( B ) 4 अरब हेक्टेयर
( C ) 8 अरब हेक्टेयर में
( D ) 5 अरब हेक्टेयर में
Ans-( B )

137. संविधान की धारा 21 का संबंध है ।
( A ) अन्य जीवों तथा प्राकृतिक संसाधनों के संरक्षण
( B ) मृदा संरक्षण
( C ) जल संसाधन संरक्षण
( D ) खनिज सम्पदा संरक्षण
Ans-( A )

138. बिहार में अति – जल – दोहन से किस तत्व का संकेन्द्रण बढ़ा है
( A ) पलोराइड
( B ) क्लोराइड
( C ) आर्सेनिक
( D ) लौह ।
Ans-( C )

139. बिहार के कितने प्रतिशत भौगोलिक क्षेत्र में बन का फैलाव है
( A ) 15 %
( B ) 20 %
( C ) 25 %
( D ) 7 %
Ans-( D )

140, भारत का राष्ट्रीय पक्षी है
( A ) कबूतर
( B ) हंस
( C ) मोर।
( D ) तोता।
Ans-( C )

141. निम्न में से कौन – सा जानवर केवल भारत में ही पाया जाता है
( A ) घड़ियाल
( B ) डॉलफिन
( C ) डेल
( D ) कछुआ ।

Ans-( A )

142. प्राकृतिक गैस किस खनिज के साथ पाया जाता है ?
( A ) यूरेनियम
( B ) पेट्रोलियम
( C ) चूना पत्थर
( D ) इनमें से कोई नहीं
Ans-( B )

143. किसका कथन है – संसाधन होते नहीं , बनते हैं ?
( A ) जिम्मरमैन
( B ) माल्थस
( C ) डार्विन
( D ) इरेटॉस्थनीज।
Ans-( A )

144. सर्वोत्तम कोयला का प्रकार कौन – सा है ?
( A ) एन्ट्रासाइट
( B ) पीट
( C ) लिग्नाइट .
( D ) बिटुमिनस
Ans-( A )

145. भारत में सर्वाधिक क्षेत्र पर किस मिट्टी का विस्तार है
( A ) जलोढ़
( B ) काली
( C ) पर्वतीय
( D ) लैटेराइट
Ans-( A )

146. तारापुर परमाणु ऊर्जा केन्द्र किस राज्य में है
( A ) मध्य प्रदेश
( B ) गुजरात
( C ) महाराष्ट्र
( D ) छत्तीसगढ़
Ans-( C )

147. भारत के किस राज्य में सौर ऊर्जा के विकास की सर्वाधिक संभावनाएं है ?
( A ) असम
( B ) अरुणाचल प्रदेश
( C ) राजस्थान
( D ) मेघालय
Ans-( C )

148. यूरेनियम का प्रमुख उत्पादक स्थल है–
( A ) डिगबोई
( B ) झरिया
( C ) घाटशिला
( D ) जादूगोडा
Ans-( D )

149. निम्न प्राकृतिक संपदाओं में किसका भंडार सीमित है ?
( A ) कोयला
( B ) हवा
( C ) मिट्टी
( D ) सौर शक्ति।
Ans-( A )

150. सीमेंट उद्योग का सबसे प्रमुख कच्चा माल क्या है ?
( A ) चूना – पत्थर
( B ) बॉक्साइट
( C ) ग्रेनाइट
( D ) लोहा।
Ans-( A )

151. अल्युमिनियम बनाने के लिए किस खनिज की आवश्यकता पड़ती है
( A ) मैंगनीज
( B ) टिन
( C ) लोहा
( D ) बॉक्साइट
Ans-( D )

152. एक टन इस्पात बनाने में कितने मैंगनीज का उपयोग होता है ?
( A ) 5 कि ० ग्रा ०
( B ) 10 कि ० ग्रा ०
( C ) 15 कि ० ग्रा ०
( D ) 20 कि ० ग्रा ०
Ans-( B )

153. कौन भारत का सबसे बड़ा लौह उत्पादक राज्य है ?
( A ) कर्नाटक
( B ) गोवा
( C ) उड़ीसा
( D ) झारखंड
Ans-( A )

154. सौर – कर्जा निम्नलिखित में कौन – सा साधन है ?

( A ) मानवकृत
( B ) पुनः पूर्ति योग्य
( C ) अजैव
( D ) चक्रीय
Ans-( A )

155. भारत में पहला परमाणु ऊर्जा स्टेशन कहाँ स्थापित हुआ ?
( A ) कलपक्कम
( B ) नरोरा
( C ) राणाप्रताप सागर
( D ) तारापुर
Ans-( D )

156. किस राज्य में खनिज तेल का विशाल भंडार है ?
( A ) असम
( B ) राजस्थान
( C ) बिहार
( D ) तमिलनाडु
Ans-( A )

157. देश के बांधों को किसने भारत का मंदिर कहा था ?
( A ) महात्मा गाँधी
( B ) जवाहरलाल नेहरू
( C ) राजेन्द्र प्रसाद
( D ) स्वामी विवेकानन्द
Ans-( B )

158. वन संरक्षण एवं प्रबंधन की दृष्टि से वनों को कितने वर्गों में बाँटा गया है ?
( A ) 2
( B ) 3
( C ) 4
( D ) 5
Ans-( B )

159.समुद्री क्षेत्र में राजनैतिक सीमा के कितने कि ० मी ० तक का क्षेत्र राष्ट्रीय सम्पदा निहित है ?
( A ) 10.2 कि ० मी ०
( B ) 15.5 कि ० मी ०
( C ) 12.2 कि ० मी ०
( D ) 19.2 कि ० मी ०
Ans-( D )

160. लौह अयस्क किस प्रकार का संसाधन है ?
( A ) नवीकरणीय
( B ) जैव

( C ) प्रवाह
( D ) अनवीकरणीय।
Ans-( D )

161. तट रेखा से कितने कि ० मी ० तक का क्षेत्र सीमा अपवर्जक आर्थिक क्षेत्र कहलाते हैं ?
( A ) 100N.M .
( B ) 200N.M .
( C ) 150N.M.
( D ) 250N.M .
Ans-( B )

162. डाकुओं की अर्थव्यवस्था का संबंध है ।
( A ) संसाधन संग्रहण से
( B ) संसाधनों के अनियोजित विदोहन से
( C ) संसाधन के नियोजित दोहन से
( D ) इनमें से कोई नहीं ।
Ans-( B )

163.स्वारीय ऊर्जा निम्नलिखित में से किस प्रकार का संसाधन है ?
( A ) पुनः पूर्ति योग्य
( B ) मानवकृत
( C ) अजैव
( D ) अचक्रीय
Ans-( A )

164. इनर्म से किस राज्य में काली मृदा पायी जाती है ?
( A ) जम्मू और कश्मीर
( B ) गुजरात
( C ) राजस्थान
( D ) झारखंड
Ans-( B )

165. काली मृदा किस फसल के लिए अधिक उपयोगी होती है ?
( A ) गेहूँ
( B ) कपास
( C ) चावल
( D ) ईख
Ans-( B )

166. डक्कन ट्रेड का निर्माण कैसे हुआ है ?
( A ) लावा के प्रवाह से
( B ) रेगुर मिट्टी से
( C ) प्राचीन जलोढक से

( D ) इनमें से कोई नहीं
Ans-( A )

167. हमारे देश का कुल क्षेत्रफल कितना है ?
( A ) 24.8 करोड़ हेक्टेयर
( B ) 28.4 करोड़ हेक्टेयर
( C ) 32.8 करोड़ हेक्टेयर
( D ) 36.4 करोड़ हेक्टेयर
Ans-( C )

168. आयु के आधार पर जलोद मृदा को कितने वर्गों में बाँटा जाता है
( A ) दो
( B ) तीन
( C ) चार
( D ) पांच।
Ans-( A )

169. लक्ष्मीसागर झील किस राज्य में स्थित है ?
( A ) मध्य प्रदेश
( B ) उत्तर प्रदेश
( C ) विहार
( D ) झारखंड
Ans-( C )

170. निम्नलिखित में से कौन लवणीय झील है ?
( A ) वूलर
( B ) डल बांटा
( C ) सांभर
( D ) गोविन्दसागर।
Ans-( C )

171. गंगा नदी पर गांधी सेतु किस शहर के निकट अवस्थित है
( A ) भागलपुर
( B ) कटिहार
( C ) पटना
( D ) गया।
Ans-( C )

172. कौन – सी नदी भ्रंश घाटी से होकर बहती है ?
( A ) महानदी
( B ) कृष्णा
( C ) तापी
( D ) तुंगभद्रा।

Ans-( C )

173. कौन – सी नदी प्रायद्वीपीय भारत की सबसे लम्बी नदी है ?
( A ) नर्मदा
( B ) गोदावरी
( C ) कृष्णा
( D ) महानदी
Ans-( B )

174. सिन्यु जल समझौता कब हुआ था ?
( A ) 1950 ई ०
( B ) 1955 ई ०
( C ) 1960 ई ०
( D ) 1965 ई ०
Ans-( C )

175. सांगपो किस नदी का उपनाम है ?
( A ) गंगा
( B ) ब्रह्मपुत्र
( C ) सतलज
( D ) गोदावरी
Ans-( B )

176. कुल जल का कितना प्रतिशत भाग महासागरों में निहित है ?
( A ) 9.5 %
( B ) 95.5 %
( C ) 96 %
( D ) 96.6 %
Ans-( D )

177. किस राज्य में वन का सबसे अधिक विस्तार है ?
( A ) केरल
( B ) कर्नाटक
( C ) मध्य प्रदेश
( D ) उत्तर प्रदेश
Ans-( C )

178.
1951 से 1980 ई ० तक लगभग कितना वर्ग किलोमीटर वन क्षेत्र कृषि भूमि में परिवर्तित हुआ ?
( A ) 30,000
( B ) 26,200
( C ) 25,200
( D ) 35,500।
Ans-( B )

179. प्राकृतिक संसाधनों के संरक्षण हेतु 1968 ई ० में कौन – सा कनवेंशन हुआ था ?
( A ) अफ्रीकी कनवेंशन
( B ) वेटलैंड्स कनवेंशन
( C ) विश्व आपदा कनवेंशन
( D ) इनमें से कोई नहीं
Ans-( B )

180. वन स्थिति रिपोर्ट के अनुसार भारत में वन का विस्तार है :
( A ) 20.60 प्रतिशत भौगोलिक क्षेत्र में
( B ) 20.55 प्रतिशत भौगोलिक क्षेत्र में
( C ) 20 प्रतिशत भौगोलिक क्षेत्र में
( D ) इनमें से कोई नहीं ।
Ans-( A )

181 . मंग्रोव्स का सबसे अधिक विस्तार है
( A ) अण्डमान – निकोबार द्वीप समूह के तटीय भाग में
( B ) सुन्दरवन में
( C ) पश्चिमी तटीय प्रदेश में
( D ) पूर्वोत्तर राज्य में
Ans-( B )

182 . टेक्सोल का उपयोग होता है ।
( A ) मलेरिया में
( B ) एड्स में
( C ) कैंसर में
( D ) टी ० बी ० के लिए।
Ans-( C )

183. ‘ चरक ‘ का सम्यन्य किस देश से था ?
( A ) म्यांमार से
( B ) श्रीलंका से
( C ) भारत से
( D ) नेपाल से
Ans-( C )

184. इनमें से कौन सी टिप्पणी प्राकृतिक वनस्पति जगत और प्राणी जगत के हास का सही कारण नहीं है ?
( A ) कृषि प्रसार
( B ) वृहत्स्तरीय विकास परियोजनाएँ
( C ) पशुचारण और ईंधन लकड़ी एकत्र करना
( D ) तीन औद्योगीकरण और शहरीकरण
Ans-( C )

185. भारत में लगभग कितने खनिज पाये जाते हैं ?
( A ) 50
( B ) 100
( C ) 150
( D ) 200
Ans-( B )

186 . छत्तीसगढ़ भारत का कितना प्रतिशत लौह – अयस्क उत्पादन करता है
( A ) 10
( B ) 20
( C ) 30
( D ) 40
Ans-( B )

187. इनमें से कौन लोहयुक्त खनिज का उदाहरण है ?
( A ) मैंगनीज
( B ) अभ्रक
( C ) बॉक्साइट
( D ) चूना – पत्थर
Ans-( A )

188. निम्नलिखित में कौन अधात्विक खनिज का उदाहरण है ?
( A ) सोना
( B ) टिन
( C ) अभ्रक
( D ) ग्रेफाइट
Ans-( C )

189. कौन लौह – अयस्क का एक प्रकार है ?
( A ) लिगनाइट
( B ) हेमाटाइट
( C ) बिटुमिनस
( D ) इनमें से सभी
Ans-( B )

190. मैंगनीज उत्पादन में भारत का विश्व में क्या स्थान है ?
( A ) प्रथम
( B ) द्वितीय
( C ) तृतीय
( D ) चतुर्थ
Ans-( C )

191. उड़ीसा किस खनिज का सबसे बड़ा उत्पादक है ?
( A ) लौह अयस्क

( B ) मैंगनीज
( C ) टिन
( D ) ताँबा
Ans-( B )

192. देश में तांबे का कुल भण्डार कितना है ?
( A ) 100 करोड़ टन
( B ) 125 करोड़ टन
( C ) 150 करोड़ टन
( D ) 175 करोड़ टन
Ans-( B )

193. बिहार – झारखण्ड में देश का कितना प्रतिशत अभ्रक का उत्पादन होता है ?
( A ) 60
( B ) 70
( C ) 80
( D ) 90
Ans-( C )

194. भारत में कोयले का सर्वप्रमुख उत्पादक राज्य है :
( A ) पश्चिम बंगाल
( B ) झारखण्ड
( C ) उड़ीसा
( D ) छत्तीसगढ़
Ans-( B )

195. ऊर्जा का गैर – पारम्परिक स्रोत है :
( A ) कोयला
( B ) विद्युत
( C ) पेट्रोलियम
( D ) सौर ऊर्जा
Ans-( D )

196. मुम्बई हाई क्यों प्रसिद्ध है ?
( A ) कोयले के निर्यात हेतु
( B ) तेल शोधक कारखाना हेतु
( C ) खनिज तेल हेतु
( D ) परमाणु शक्ति हेतु
Ans-( C )

197. भारत का प्रथम तेल शोधक कारखाना कहाँ स्थित है ?
( A ) मथुरा
( B ) बरौनी
( C ) डिगबोई

( D ) गुवाहाटी
Ans-( C )

198. भाखड़ा नंगल परियोजना किस नदी पर अवस्थित है ?
( A ) नर्मदा
( B ) झेलम
( C ) सतलज
( D ) व्यास
Ans-( C )

199. दक्षिण भारत की सबसे बड़ी नदीघाटी परियोजना है :
( A ) तुंगभद्रा
( B ) इरावती
( C ) चंबल
( D ) हीराकुंड
Ans-( A )

200. ताप विद्युत केन्द्र का उदाहरण है
( A ) गया
( B ) बरौनी
( C ) समस्तीपुर
( D ) कटिहार
Ans-( B )

201 . एशिया का सबसे बड़ा परमाणु विद्युत गृह है
( A ) तारापुर
( B ) कलपक्कम
( C ) नारौरा
( D ) कैगा
Ans-( A )

202. ज्वारीय एवं तरंग ऊर्जा उत्पादन हेतु भारत में अधिक अनुकूल परिस्थितियाँ कहाँ पायी जाती हैं ?
( A ) मन्नार की खाड़ी में
( B ) खम्भात की खाड़ी में
( C ) गंगा नदी में
( D ) कोसी नदी में
Ans-( B )

203. कौन – सा ऊर्जा खोत अनवीकरणीय है ?
( A ) जल
( B ) सौर
( C ) कोयला

( D ) पवन
Ans-( C )

204. प्राथमिक ऊर्जा का उदाहरण नहीं है ?
( A ) कोयला
( B ) विद्युत
( C ) पेट्रोलियम
( D ) प्राकृतिक गैस
Ans-( B )

205 . गोण्डवाना समूह के कोयले का निर्माण हुआ था
( A ) 20 करोड़ वर्ष पूर्व
( B ) 20 लाख वर्ष पूर्व
( C ) 20 हजार वर्ष पूर्व
( D ) इनमें से कोई नहीं
Ans-( B )

206. गोंडवाना समूह में भारत का कितना प्रतिशत कोयला भंडारित है ?
( A ) 90 प्रतिशत
( B ) 92 प्रतिशत
( C ) 94 प्रतिशत
( D ) 96 प्रतिशत
Ans-( D )

207 . ग्रेफाइट को और किस नाम से जाना जाता है
( A ) जिप्सम
( B ) थोरियम
( C ) प्लबगो
( D ) इनमें से कोई नहीं
Ans-( C )

208. आधुनिक सभ्यता की रीढ़ क्या है ?
( A ) तांबा
( B ) सोना
( C ) लोहा
( D ) मैंगनीज।
Ans-( C )

209. ‘ नर्मदा बचाओ अभियान ‘ किसने चलाया ?
( A ) मेधा पाटेकर
( B ) अन्ना हजारे
( C ) संदीप पाण्डेय
( D ) इनमें से कोई नहीं
Ans-( A )

210. किसी देश के आर्थिक विकास का मेरुदंड क्या होता है ?
( A ) संसाधन
( B ) ऊर्जा
( C ) खनिज
( D ) जल।
Ans-( A )

211. राष्ट्रीय जल नीति भारत में कब लागू हुई ?
( A ) 2000 में
( B ) 2002 में
( C ) 2004 में
( D ) 2006 में
Ans-( A )

212. भारत में कितने प्रकार की मृदा पायी जाती है ?
( A ) दो
( B ) चार
( C ) छह
( D ) आठ है ?
Ans( C )

213. संसाधन के रूप में किसी पदार्थ का अस्तित्व किस पर निर्भर करता है
( A ) मात्रा पर
( B ) उपयोगिता पर
( C ) मूल्य पर
( D ) मूल्यांकन पर
Ans-( B )

214. सबसे बड़े जल संग्रहण केन्द्र कौन होते हैं ?
( A ) तालाब
( B ) झील
( C ) महासागर
( D ) कुआँ
Ans-( C )

215. निम्नलिखित में कौन प्रवहनीय संसाधन है ?
( A ) नदी
( B ) कोयला
( C ) वन
( D ) पहाड़
Ans-( A )

216. नवगांव तेल उत्पादक क्षेत्र किस राज्य में है ?
( A ) मेघालय
( B ) मणिपुर
( C ) गुजरात
( D ) नागालैण्ड
Ans-( C )

217, ‘ सरदार सरोवर बांध ‘ किस नदी पर है ?
( A ) कृष्णा
( B ) नर्मदा
( C ) गोदावरी
( D ) कावेरी
Ans-( B )

218. 1992 में रियो – डी – जेनेरो में कौन – सा सम्मेलन हुआ था ?
( A ) पृथ्वी
( B ) जनसंख्या
( C ) जलवायु
( D ) महाद्वीपीय
Ans-( A )

219. पर्यावरण संरक्षण हेतु प्रथम विश्व शिखर सम्मेलन कहाँ हुआ था
( A ) पेरिस
( B ) स्टॉकहोम
( C ) मास्को
( D ) न्यूयार्क
Ans-( B )

220 . द्वितीय पृथ्वी सम्मेलन कब और कहाँ हुआ था ?
( A ) 1995 , पेरिस
( B ) 1996 , मास्को
( C ) 1997 , न्यूयार्क
( D ) 1998 , लंदन
Ans-( C )

221. तृतीय पृथ्वी सम्मेलन कब और कहाँ हुआ था ?
( A ) 2002 , जोहांसबर्ग
( B ) 2003 , बीजिंग
( C ) 2004 , ढाका
( D ) 2005 , कोलम्बो
Ans-( A )

222. भारत में कितनी भूमि बंजर भूमि के रूप में ?

( A ) एक चौथाई
( B ) एक तिहाई
( C ) आधा
( D ) इनमें से कोई नहीं .
Ans-( A )

223 . वॉल्ड वाइड फॉर मैचर के अनुसार भारत में कितनी भूमि निम्नीकृत हो चुकी है ?
( A ) 10 करोड़ हेक्टेयर
( B ) 12 करोड़ हेक्टेयर
( C ) 13 करोड़ हेक्टेयर
( D ) 15 करोड़ हेक्टेयर
Ans-( C )

224. मृदा संरक्षण के लिए कौन – उपाय उपयोगी है ?
( A ) खेतों में डायूमस डालना
( B ) पशु – चारण पर नियंत्रण
( C ) समोच्चरेखीय जुताई
( D ) उपर्युक्त सभी।
Ans-( D )

225. मृदा संरचना में मूल बट्टान के ऊपर कितनी परतें होती है ?
( A ) दो
( B ) तीन
( C ) चार
( D ) छः
Ans-( B )

226. ‘ लिमिटेड टू ग्रोथ ‘ पुस्तक किस वर्ष प्रकाशित ?
( A ) 1970 में
( B ) 1972 में
( C ) 1974 में
( D ) 1976 में।
Ans-( B )

227. बुन्दलैंड कमीशन ने सतत् पोषणीय विकास ‘ की अवधारणा क्रय प्रस्तुत की ?
( A ) 1985 में
( B ) 1986 में
( C ) 1987 में
( D ) 1988 में
Ans-( C )

228. संसार में सबसे कीमती संसाधन किसे माना जाता है ?
( A ) खनिज
( B ) कच्चा तेल

( C ) पहाड़
( D ) इनमें से कोई नहीं
Ans-( B )

229 . साल किस वन का वृक्ष है ?
( A ) पतझड़
( B ) डेल्याई
( C ) सदाबहार
( D ) शुष्क
Ans-( A )

230. कंचनजंघा जीवमंडल रिसर्च किस राज्य में है ?
( A ) बिहार
( B ) उत्तर प्रदेश
( C ) सिक्किम
( D ) उत्तरांचल
Ans-( C )

231. किस राज्य में जैविक मिट्टी नहीं पायी जाती है
( A ) झारखंड
( B ) उड़ीसा
( C छत्तीसगढ़
( D ) कर्नाटक
Ans-( A )

232. पीतल बनाया जाता है
( A ) जस्ता से
( B ) जस्ता , तांबा और टीन से
( C ) ताँबा और जस्ता से
( D ) तांबा से
Ans-( C )

233. बैलाडिला खान से कौन – सा खनिज निकाला जाता है ?
( A ) ताँबा
( B ) सोना
( C ) हीरा
( D ) लौह आयस्क
Ans-( D )

234. भारत में किस बंदरगाह से लोहे का नियांत किया जाता है ?
( A ) चेन्नई
( B ) विशाखापट्टनम्
( C ) कांडला

( D ) मुम्बई
Ans-( B )

235.प्लाई बुद्ध का निर्माण सर्वप्रथम कहाँ हुआ ?
( A ) जर्मनी
( B ) चीन
( C ) भारत
( D ) फ्रांस
Ans-( A )

236.भैसालोटन बाँध किस नदी पर बनाया गया है ।
( A ) बागमती
( B ) गंडक
( C ) कोशी
( D ) सोन
Ans-( B )

237.दामोदर पाटी योजना का निर्माण का सर्वाधिक महत्त्वपूर्ण कारण क्या था ?
( A ) सिंचाई की व्यवस्था करना
( B ) बादों पर नियंत्रण रखना
( C ) मत्स्य पालन करना
( D ) उपर्युक्त सभी
Ans-( D )

238. भारत का पहला जल विद्युत संयंत्र कहाँ लगाया गया ?
( A ) सिक्किम
( B ) कोसी
( C ) भटिंडा
( D ) दार्जिलिंग
Ans-( A )

239. निम्नलिखित में से कौन अधात्विक खनिज का उदाहरण है
( A ) सोना
( B ) टिन
( C ) अधक
( D ) ग्रेफाइट
Ans-( C )

240 . जामनगर तेल शोषक कारखाना किस राज्य में है ?
( A ) विहार
( B ) असम
( C ) गुजरात
( D ) महाराष्ट्र
Ans-( C )

241 . कैगा परमाणु ऊर्जा उत्पादक केन्द्र किस राज्य में है ?
( A ) तमिलनाडु
( B ) कर्नाटक
( C ) आंध्र प्रदेश
( D ) केरल
Ans-( B )

242. किसी राष्ट्र सा सबसे महत्त्वपूर्ण संसाधन कौन है ?
( A ) खनिज
( B ) जल
( C ) मानव
( D ) पहाड़
Ans- ( C )

243.एशिया का सबसे बड़ा परमाणु विद्युत गृह है
( A ) तारापुर
( B ) कलपक्कम
( C ) नरौरा
( D ) कैगा
Ans- ( A )

244. केरल में किस मिट्टी की प्रधानता है ?
( A ) लाल
( B ) लैटेराइट
( C ) जलोढ़
( D ) बलुई
Ans- ( B )

245 . बांगर मिट्टी किसे कहा जाता है ?
( A ) पुरानी जलोढ़
( B ) नवीन जलोढ़
( C ) लैटेराइट
( D ) बंजर
Ans-( A )

246. गुजरात में भूमि निम्नीकरण का प्रमुख कारण क्या है ?
( A ) सिंचाई का प्रभाव
( B ) नमक का प्रभाव
( C ) बाल का प्रभाव
( D ) तूफान का प्रभाव
Ans-( B )

247 . जालोष मिट्टी में किसकी मात्रा कम होती है ?
( A ) नाइट्रोजन
( B ) जीवांश
( C ) ‘ क ‘ एवं ‘ ख ‘ दोनों
( D ) सभी गलत
Ans-( C )

248 . राजस्थान की सबसे महत्वपूर्ण परियोजना कौन सी है ?
( A ) चंबल
( B ) नागार्जुनसागर
( C ) इंदिरा गांधी नगर
( D ) भाबड़ा नंगल
Ans-( A )

249. सारे जल की सबसे बड़ी झील कौन है
( A ) मृतसागर
( B ) बैकाल
( C ) चिल्का
( D ) इनमें से कोई नहीं
Ans-( A )

250. बांस ड्रिप सिंचाई प्रणाली किस राज्य में प्रचलित है ?
( A ) उड़ीसा
( B ) मेघालय
( C ) तमिलनाडु
( D ) गुजरात
Ans-( B )

251. इन्द्रपुरी पराग किस परियोजना के अन्तर्गत बना है ?
( A ) नर्मदा घाटी परियोजना
( B ) सोन परियोजना
( C ) चंबल घाटी परियोजना
( D ) कोशी परियोजना
Ans-( B )

252. कोशी परियोजना में किस स्थान पर बराज बनाया गया है ?
( A ) हनुमान नगर
( B ) राजेन्द्र नगर
( C ) इंदिरा नगर
( D ) जगजीवन नगर
Ans-( A )

253 . बलूत किस वन की विशेषता है ।
( A ) पर्वतीय
( B ) शुष्क

( C ) डेल्टाई
( D ) सदावहार
Ans-( A )

254. भारत का राष्ट्रीय पशु कौन है ?
( A ) बैल
( B ) शेर
( C ) भालू
( D ) बाय
Ans-( D )

255 . सदाबहार बन भारत के किस क्षेत्र में पाया जाता है ?
( A ) दक्षिण पूर्व
( B ) उत्तर पश्चिम
( C ) उत्तर पूर्व
( D ) दक्षिण मध्य
Ans-( C )

256. बिजली के बल्य के फिलामेट बनाने में किस धातु का उपयोग होता है ?
( A ) तांचा
( B ) एल्युमिनियम
( C ) टंग्स्टन
( D ) कोबाल्ट
Ans-( C )

257. प्लास्टर ऑफ पेरिस किससे बनाया जाता है ?
( A ) डोलोमाइट
( B ) जिप्सम
( C ) प्लैटिनम
( D ) कायनाइट
Ans-( B )

258 . अमझोर किस खनिज उत्पादन के लिए प्रसिद्ध है ?
( A ) पाइराइट
( B ) अभ्रक
( C ) क्वार्टजाइट
( D ) चूना पत्थर
Ans-( A )

259 . ‘ काला हीरा ‘ किसे कहा जाता है ?
( A ) ग्रेफाइट
( B ) ग्रीस
( C ) कोयला
( D ) मोबिल

Ans-( C )

260. मुम्बई हाई क्या है ?
( A ) एक ऊँची सड़क
( B ) एक हवाई अड्डा
( C ) खनिज तेल उत्पादक क्षेत्र
( D ) इनमें कोई नहीं
**Ans-( C )**

261. तारापुर परमाणु ऊर्जा केंद्र
(A) गुजरात में
(B) मध्य प्रदेश में
(C) छत्तीसगढ़ में
(D) महाराष्ट्र में
Ans:-(D)

262. भारत का पहला परमाणु ऊर्जा केन्द्र कहाँ स्थितहै?
(A) तारापुर
(B) नरौरा
(C) कलपक्कम
(D) राणाप्रताप सागर
Ans:-(A)

263. ताप विद्युत केन्द्र का उदाहरण है।
(A) गया
(B) बरौनी
(C) समस्तीपुर
(D) कटिहार
Ans:-(B)

264. पवन ऊर्जा निम्नलिखित में से कौन-सा संसाधनहै?
(A) मानव निर्मित
(B) अनवीकरणीय
(C) नवीकरणीय
(D) जैव
Ans:-(C)

265. विश्व में सबसे अधिक पवन ऊर्जा का दोहन किस देश में होता है?
(A) आस्ट्रेलिया
(B) इंग्लैंड

(C) नीदरलैंड
(D) जापान
Ans:-(C)

PLEASE SHARE THIS

YOU MIGHT ALSO LIKE

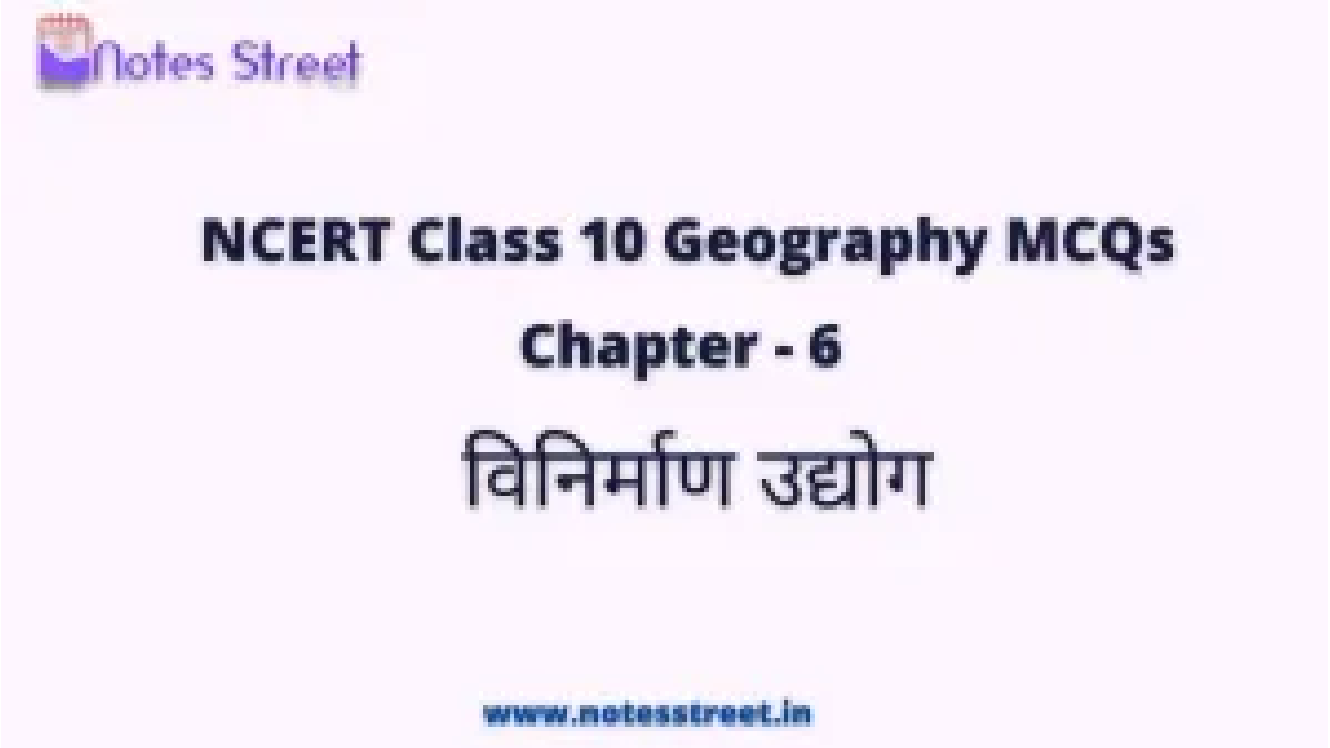


**NCERT Class 10 Geography MCQs Chapter – 6 विनिर्माण उद्योग**

April 8, 2022

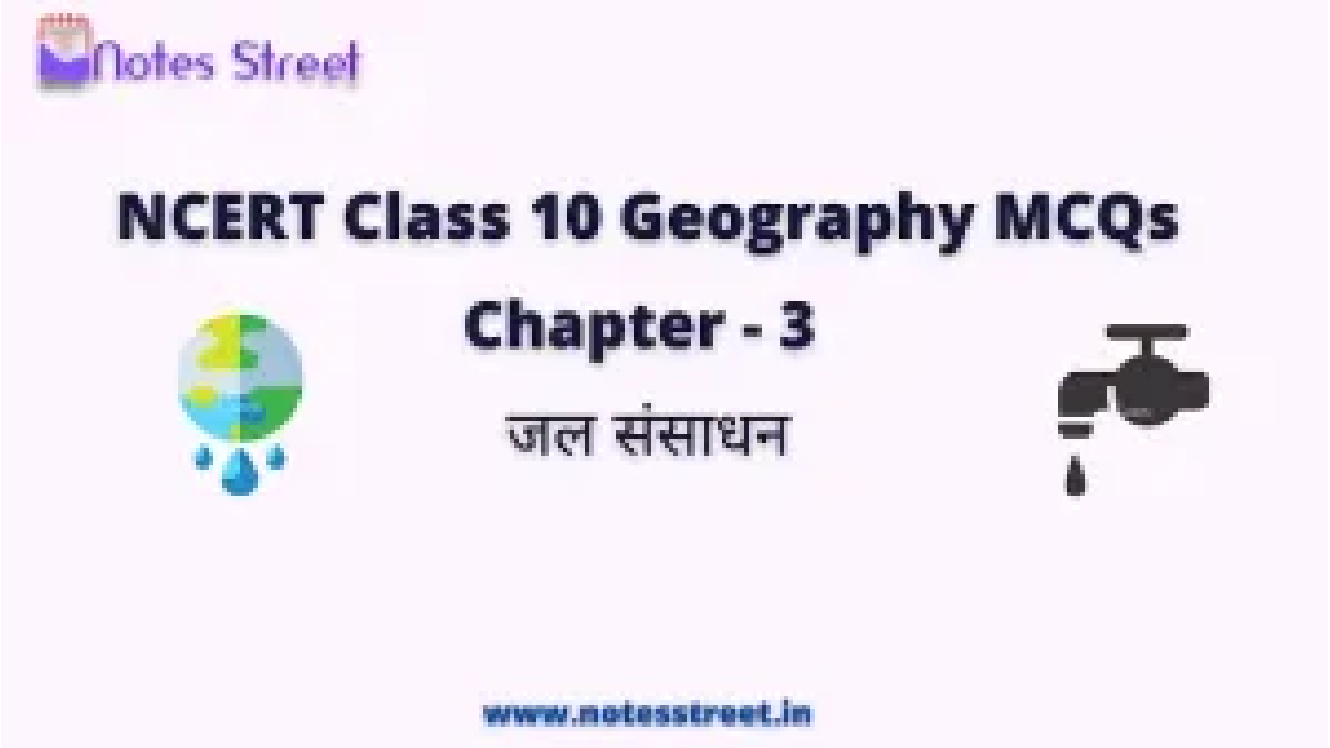


**NCERT Class 10 Geography MCQs Chapter – 3 जल संसाधन**

October 23, 2021

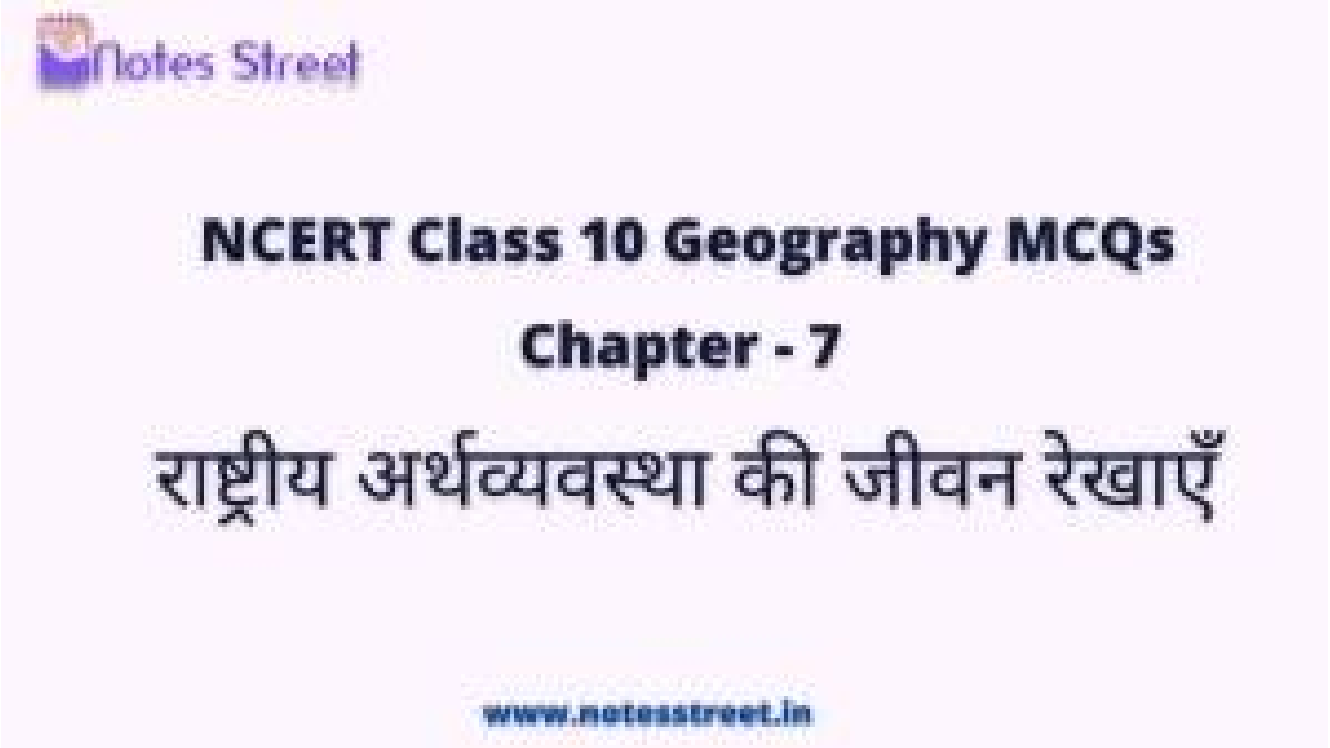


**NCERT Class 10 Geography MCQs Chapter – 7 राष्ट्रीय अर्थव्यवस्था की जीवन रेखाएँ**

April 8, 2022