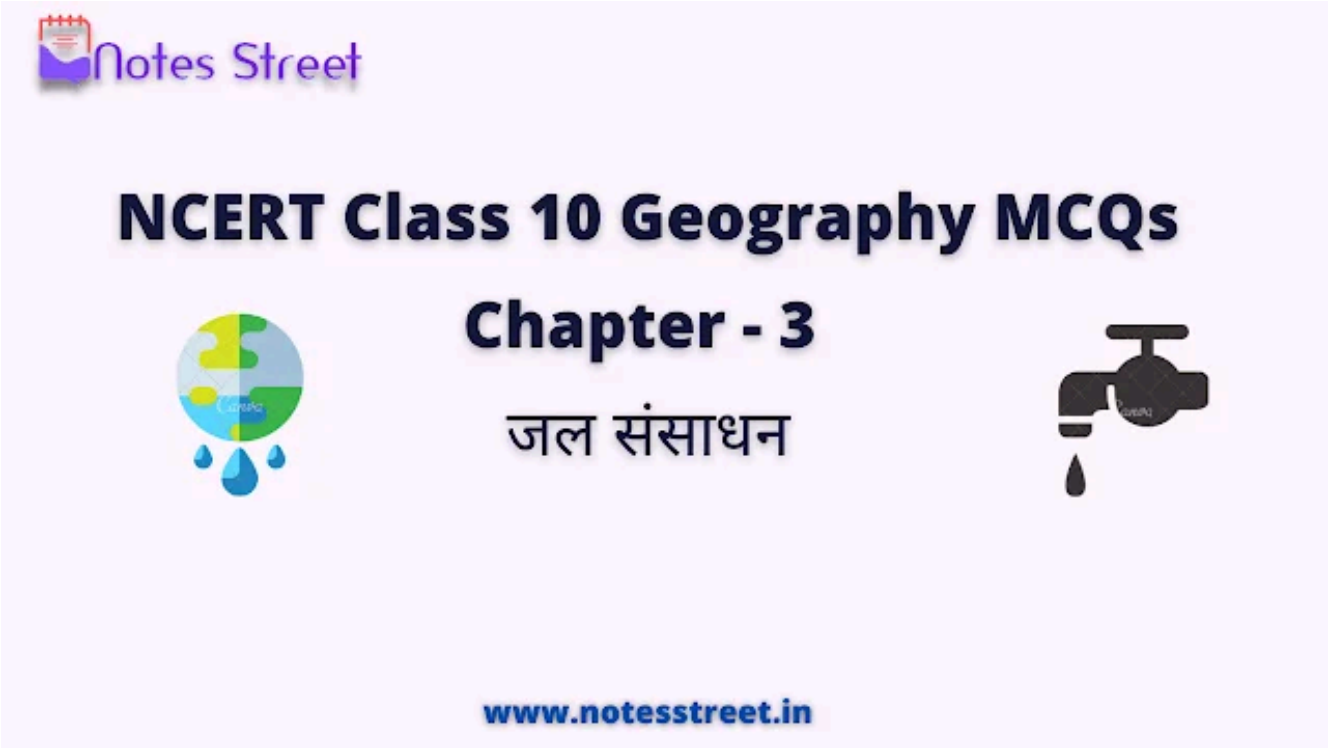


NCERT Class 10 Geography MCQs Chapter - 3 जल संसाधन

NCERT Class 10 Geography MCQs

NCERT Class 10 Geography MCQs Chapter – 3 जल संसाधन

1. जल प्रदूषण के कारण निम्न में से कौन सी समस्या उत्पन्न होती है?
(a) जलाशय में तलछट का जमाना
(b) जल जनित बीमारियाँ
(c) औद्योगिक कचरे का निर्वहन
(d) जलीय जीवन के बढ़ने में
Ans( b )

2. निम्नलिखित में से कौन आज भारत में उत्पादित कुल बिजली का लगभग 22 प्रतिशत है?
(a) सौर ऊर्जा
(b) जल विद्युत
(c) उद्योग
(d) भूतापीय ऊर्जा
Ans( b )

3. इनमें से कौन 11वीं शताब्दी में निर्मित प्राचीन भारत की सबसे बड़ी कृत्रिम झीलों में से एक है?
(a) गोविंदसागर झील

(b) हॉज खास
(c) भोपाल झील
(d) डल झील
Ans( c )

4. इनमें से कौन सी जलीय कृतियाँ प्राचीन काल की विशेषता नहीं है?
(a) बहुउद्देशीय नदी घाटीपरियोजनाएँ
(b) पत्थर के मलबे से बने बांध
(c) जलाशय या झीलें
(d) तटबंध और नहरें
Ans( a )

5. खारे जल की सबसे बड़ी झील कौन है?
(a) बैकाल
(b) लोनार
(c) कैस्पियन
(d) मृतसागर
Ans: (a)

6. पृथ्वी का कितना भाग जल से घिरा हुआ है?
(a) तीन चौथाई
(b) दो तिहाई
(c) एक चौथाई
(d) तीन तिहाई
Ans: (a)

7. मीठे जल की सबसे बड़ी झील कौन है?
(a) कैस्पियन
(b) टिटिकाका
(c) बैकाल
(d) सुपीरियर
Ans: (d)

8. सरदार सरोवर बांध किस नदी पर बनाया गया है?
(a) कृष्णा नदी
(b) नर्मदा नदी
(c) कावेरी नदी
(d) महानदी
Ans: (b)

9. सबसे गहरी खारे जल की झील कौन है?
(a) मृतसागर
(b) बैकाल
(c) चिल्का
(d) ह्यूरन
Ans: (a)

10. भारत में सिंचाई के प्रमुख साधन है?
(a) नहरे
(b) तलाब
(c) कुएँ और नलकूप
(d) उपयुक्त सभी
Ans: (d)

11. निम्नलिखित में से कौन सी बहुउद्देशीय परियोजना सतलुज-ब्यास नदी बेसिन में पाई जाती है?
(a) हीराकुंड परियोजना
(b) दामोदर घाटी परियोजना
(c) भाखड़ा नांगल परियोजना
(d) रिहंद परियोजना
Ans( c )

12. निम्नलिखित में से किस नदी पर हीराकुंड बाँध का निर्माण किया गया है?
(a) सतलुज
(b) ब्यास
(c) महानदी
(d) नर्मदा
Ans( c )

13. कुल उपलब्ध जल में पीने लायक जल कितना है?
(a) 70%
(b) 2.5%
(c) 29%
(d) 96%
Ans: (b)

14. भारत का पहला जल विद्युत केंद्र कहां स्थापित किया गया था?
(a) पंजाब
(b) 'उड़ीसा
(c) राजस्थान नर्मदा नदी पर
(d) गुजरात में कावेरी नदी पर

Ans: (d)

15. मीठे जल की सबसे ऊँची झील का क्या नाम है?
(a) टिटिकाका
(b) बैकाल
(c) विनिपेग
(d) विंडसर
Ans: (a)

16.महानदी बेसिन पर निर्मित बहुउद्देशीय परियोजना है?
(a) हीराकुंड परियोजना
(b) सलाल परियोजना
(c) सरदार सरोवर परियोजना
(d) मेट्टूर परियोजना
Ans: (a)

17. इनमें राजस्थान की सबसे महत्वपूर्ण परियोजना कौन-सी है?
(a) चंबल
(b) नागार्जुन सागर
(c) इंदिरा गाँधी नगर
(d) भाखड़ा-नांगल
Ans: (c)

18. निम्नलिखित में से किन नदियों के जल ग्रहण क्षेत्र बहुत बड़े हैं ?
(a) गंगा
(b) ब्रह्मपुत्र
(c) सिन्धु
(d) उपरोक्त सभी
Ans- ( c )

19. निम्न में से कौन सा राज्य अपने भौम जल का उपयोग क्षमता से कम करता है ?
(a) छतीसगढ़
(b) राजस्थान
(c) पंजाब
(d) हरियाणा
Ans- ( a )

20. निम्न में से किस राज्य में लैगून और झीलों का प्रयोग धरातलीय जल संसाधन के रूप में होता है ?
(a) उड़ीसा
(b) केरल

(c) A तथा B दोनों
(d) पंजाब
Ans- ( c )

21.निम्न में से कौन सा जल प्रदुषण का एक स्त्रोत है ?
(a) नगरीय वाही जल
(b) नाभिकीय ऊर्जा संयंत्र
(c) वाहित माल
(d) उपरोक्त सभी
Ans- ( d )

22. निम्न में से भारत के किस राज्य में नीरू-मीरू कार्यक्रम चलाया गया ?
(a) कर्नाटक
(b) आंध्रप्रदेश
(c) केरल
(d) तमिलनाडु
Ans- ( b )

23. निम्न में से किस राज्य में अरवारी पानी संसद कार्यक्रम चलाया गया ?
(a) हरियाणा
(b) पंजाबा
(c) राजस्थान
(d) उत्तरप्रदेश
Ans- ( c )

24.निम्न में से कौन सा जल संभर कार्यक्रम केंद्र सरकार द्वारा चलाया गया ?
(a) हरियाली
(b) A तथा B दोनों
(c) इनमे से कोई नहीं
Ans- ( b )

25. निम्न में से कौन से वर्षा जल संग्रहण ढाँचे  का निर्माण राजस्थान में किया जाता है ?
(a) तालाब
(b) जोहड़
(c) कुंड
(d) पाश्व जल
Ans- ( c )

26.. बाँधो को आधुनिक भारत के मंदिर किसने कहा था?
(a) जवाहरलाल नेहरू ने

(b) भीमराव अंबेडकर ने
(c) इंदिरा गांधी ने
(d) महात्मा गांधी ने
Ans: (a)

27. इनमें किस परियोजना का मुख्य उद्देश्य बाढ़ नियंत्रण रहा है?
(a) चंबल
(b) कोसी
(c) भाखड़ा
(d) हीराकुंड
Ans: (b)

28. सरदार सरोवर बांध किस राज्य में स्थित है?
(a) मेघालय
(b) राजस्थान
(c) गुजरात
(d) कर्नाटक
Ans: (c)

29.. विश्व के कुल जल का कितना प्रतिशत महासागरों में पाया जाता है?
(a) 96.5%
(b) 90%
(c) 71%
(d) 98%
Ans: (a)

30. महा नदी पर स्थित बहुउद्देशीय परियोजना का नाम है?
(a) दामोदर घाटी परियोजना
(b) हीराकुंड परियोजना
(c) सलाल परियोजना
(d) भाखड़ा नांगल परियोजना
Ans : (b)

31. प्रतिव्यक्ति प्रतिवर्ष जल उपलब्धता की दृष्टि से भारत का विश्व में कौन-सा स्थान है?
(a) 182वाँ
(b) 157वाँ
(c) 101वाँ
(d) 133वाँ
Ans: (d)

32. भारत का वह कौन सा राज्य है जहां पूरे राज्य में प्रत्येक घर में छत वर्षा जल संग्रहण ढांचो का बनाना आवश्यक कर दिया है?
(a) केरल
(b) तमिलनाडु
(c) कर्नाटक
(d) आंध्रप्रदेश
Ans: (b)

33. राजस्थान में छत वर्षा जल संग्रहण को कहा जाता है?
(a) गुल
(b) कुल
(c) टाँका
(d) बाओक्स
Ans( c )

34. प्रतिव्यक्ति प्रतिवर्ष जल उपलब्धता की दृष्टि से विश्व में भारत का कौन-सा स्थान है?
(a) 182वाँ
(b) 100वाँ
(c) 150वाँ
(d) 133वाँ
Ans: (d)

35. देश में सर्वाधिक वर्षा कहाँ होती है?
(a) पूर्णिया
(b) मासिनराम
(c) चेरापूँजी
(d) कोच्चि
Ans: (b)

36. देश की कुल विद्युत का कितना हिस्सा जलविद्युत से प्राप्त होता है?
(a)10%
(b) 45%
(c) 15%
(d) 17.39%
Ans: (d)

38.भारत में जल का सबसे अधिक उपयोग किया जाता है।
(a) सिंचाई में
(b) उद्योग में
(c) घरेलू उपयोग में

(d) व्यापार में
उत्तर : (a )

39. वर्षाजल संग्रहण ढाँचा हर घर में बनाना किस राज्य में कानूनन अनिवार्य है?
(a) बिहार
(b) तमिलनाडु
(c) राजस्थान
(d) कर्नाटक
Ans: (b)

40. भारत के किस भाग में तलाब का सिंचाई के लिए सिंचाई के साधन के रूप में सर्वाधिक प्रयोग होता है?
(a) पश्चिमी
(b) पूर्वी
(c) दक्षिणी
(d) उत्तरी
Ans: (c)

41.देश में कुल पुनः पूर्ती योग्य भौम जल संसाधन लगभग ___ घन किलोमीटर हैं
(a) 400
(b) 599
(c) 432
(d) 129
Ans – ( c )

42. निम्न में से किस राज्य में जल संग्रहण संरचना आवश्यक है ?
(a) हिमाचल प्रदेश
(b) उत्तर प्रदेश
(c) तमिलनाडु
(d) केरल
Ans- ( c )

43. निम्न में से जल किस प्रकार का संसाधन है ?
(a) अजैव
(b) जैव
(c) अनवीकरणीय
(d) चक्रीय
Ans- ( d )

44.पृथ्वी का लगभग ____ धरातल पानी से आच्छादित है ?

(a) 50%
(b) 71%
(c) 40%
(d) 29%
Ans- ( b )

45. निम्नलिखित राज्यों में से कौन सा भौम जल का सर्वाधिक उपयोग करता है ?
(a) पंजाब
(b) हरियाणा
(c) हिमाचल प्रदेश
(d) A तथा B दोनों
Ans- ( d )

46. विश्व के कुल जल संसाधन का कितना भारत में उपलब्ध है।
(a) 16%
(b) 10%
(c) 4%
(d) 1%
Ans: (c)

47. गंडक परियोजना कहाँ विकसित है?
(a) बिहार
(b) उड़ीसा
(c) उत्तर प्रदेश
(d) झारखंड
उत्तर : (a)

48. चंबल परियोजना के अंतर्गत तीन बाँध-गाँधी सागर, राणापता सागर कहाँ बनाए गए हैं?
(a) भागलपुर
(b) कोटा
(c) जयपुर
(d) अहमदाबाद
उत्तर : (b)

49. निम्नलिखित दक्षिण भारतीय राज्यों में से किस राज्य में भूमिगत जल उपयोग इसके कुल भूमिगत जल संभाव्य से अधिक है?
(a) आन्ध्र प्रदेश
(b) केरल
(c) तमिलनाडु
(d) कर्नाटक

उत्तर : (c)

50. घन किलोमीटर में दी गई निम्नलिखित संख्याओं में से कौन-सी संख्या भारत में कुल वार्षिक वर्षा दर्शाती है?

(a) 5,000

(b) 3,000

(c) 2,000

(d) 4,000

उत्तर : (d)

51.वर्षण से प्राप्त जल कैसा होता है ?

(a) अलवणीय

(b) लवणीय

(c) पृष्ठीय

(d) इनमे से कोई नहीं

Ans- ( a )

52.देश में प्रयुक्त कुल जल का सबसे अधिक समानुपात निम्न सेक्टरों में से किसका है ?

(a) उद्योग

(b) घरेलु उपयोग

(c) सिंचाई

(d) इनमे से कोई नहीं

Ans- ( c )

53.निम्नलिखित दक्षिण भारतीय राज्यों में से किस राज्य में भौम जल उपयोग इसके कुल भौम जल संभाव्य से ज्यादा है ?

(a) कर्नाटक

(b) केरल

(c) आंध्र प्रदेश

(d) तमिलनाडु

Ans- ( d )

54.भारतीय राष्ट्रीय जल नीति के सन्दर्भ में कौन सा कथन सत्य है ?

(a) पेयजल सभी प्राणियों को उपलब्ध करवाना प्राथमिकता

(b) जल के सभी विविध प्रयोगों में कार्य क्षमता में सुधार

(c) भौम जल के शोषण को सीमित किया जाए

(d) उपरोक्त सभी

Ans- ( d )

55.घन किलोमीटर में दी गई निम्नलिखित संख्याओं में से कौन सी संख्या भारत के कुल वार्षिक वर्षा को दर्शाती है ?

(a) 5000

(b) 2000

(c) 3000

(d) 4000

Ans- ( d )

56. जल संभार प्रबंधन :

(a) धरातलीय जल संसाधन का दक्ष प्रबंधन

(b) भौम जल का दक्ष प्रबंधन

(c) A तथा B दोनों

(d) इनमे से कोई नहीं

Ans- ( c )

57.यमुना नदी किन दो शहरों के बीच सबसे अधिक प्रदूषित होती है ?

(a) हरियाणा और पंजाब

(b) दिल्ली और इटावा

(c) जयपुर और जोधपुर

(d) इनमे से कोई नहीं

Ans- ( b )

58. निम्न में से अहमदाबाद में सबसे प्रदूषित नदी कौन सी है ?

(a) गंगा

(b) यमुना

(c) साबरमती

(d) इनमे से कोई नहीं

Ans- ( c )

59. कानपुर तथा वाराणसी से सबसे प्रदूषित नदी कौन सी है ?

(a) गंगा

(b) यमुना

(c) साबरमती

(d) गोमती

Ans- ( a )

60. लखनऊ में निम्न में से कौन सी नदी सर्वाधिक प्रदूषित है ?

(a) गंगा

(b) गोमती

(c) यमुना

(d) साबरमती
Ans- ( b )

61. निम्नलिखित नदियों में से किस नदी में सबसे ज्यादा पुन: प्रतियोग्य भूमिगत जल-संसाधन है?
(a) गोदावरी
(b) गंगा
(c) ब्रह्मपुत्र
(d) सिंधु
Ans: (c )

62. इनमें किस परियोजना का प्रमुख उद्देश्य बाढ़-नियंत्रण रहा है?
(a) कोसी
(b) हीराकुंड
(c) भाखड़ा-नांगल
(d) चंबल
Ans: (a)

63. राष्ट्रीय जलनीति किस वर्ष घोषित की गई थी?
(a) 1997
(b) 1983
(c) 1987
(d) 1990
Ans: (c )

64. महासागरों में कुल जल की कितनी मात्रा है?
(a) 94%
(b) 71%
(c) 29%
(d) 96.5%
Ans: (d )

65. इंद्रपुरी जलाशय परियोजना किस राज्य में है?
(a) बिहार
(b) छत्तीसगढ़
(c) केरल
(d) असम
Ans: (a)

66.प्राणियों के शरीर में कितना प्रतिशत जल की मात्रा निहित होती है?
(a) 10%

(b) 35%
(c) 45%
(d) 65%
उत्तर: (d)

67. निम्नलिखित में से कौन सा पर्यावरणीय नुकसान बहुउद्देशीय परियोजनाओं के कारण नहीं होता है?
(a) जल जनित बीमारियाँ और कीट
(b) जल के अत्यधिक उपयोग से उत्पन्न प्रदूषण
(c) भूकंप
(d) ज्वालामुखी गतिविधि
Ans( d )

68. इनमें से किस क्षेत्र में 'गुल' और 'कुल' का उपयोग कृषि के पानी के उपयोग के लिए किया जाता है?
(a) दक्षिणी पठार
(b) राजस्थान के रेगिस्तान
(c) पश्चिमी हिमालय
(d) गंगा का मैदान
Ans( c )

69. निम्न में से किन कारणों से 'छत वर्षा जल संग्रहण' खासकर राजस्थान में आमतौर पर की जाती है?
(a) सिंचाई के लिए पानी का भंडारण करने के लिए
(b) घर को ठंडा रखने के लिए
(c) पीने के पानी को संग्रहित करने के लिए
(d) छतों की सफाई करने के लिए
Ans( c )

70. वृहद् क्षेत्र में जल की उपस्थिति के कारण ही पृथ्वी को कहते हैं
(a) उजला ग्रह
(b) नीला ग्रह
(c) लाल ग्रह
(d) हरा ग्रह
Ans: (b)

71. कुल जल का कितना प्रतिशत भाग महासागरों में निहित है?
(a) 9.5%
(b) 95.5%
(c) 96%
(d) 96.6%
Ans: (d)

72. देश के बाँधों को किसने 'भारत का मन्दिर' कहा था?
(a) महात्मा गाँधी
(b) डॉ. राजेन्द्र प्रसाद
(c) पंडित नेहरू
(d) स्वामी विवेकानन्द
Ans: (c )

73. बिहार में अति-जल-दोहन से किस तत्त्व का संकेन्द्रण बढ़ा है?
(a) फ्लोराइड
(b) क्लोराइड
(c) आर्सेनिक
(d) लौह
Ans: (c )

74. जल किस प्रकार का संसाधन है?
(a) चक्रीय संसाधन
(b) जैव संसाधन
(c) अजैव संसाधन
(d) अनवीकरणीय संसाधन
Ans: (a)

75. भारत में प्रयुक्त कुल जल का सबसे अधिक समानुपात किस क्षेत्र में है?
(a) उद्योग
(b) सिंचाई
(c) घरेलू उपयोग
(d) इनमें कोई नहीं
Ans: (b)

76. पृथ्वी का कितना प्रतिशत भाग धरातल जल से आच्छादित है?
(a) 70 प्रतिशत
(b) 71 प्रतिशत
(c) 69 प्रतिशत
(d) 65 प्रतिशत
Ans: (b)

77. निम्नलिखित में से किस राज्य में बाँस ड्रिप सिंचाई प्रणाली प्रचलित है?
(a) राजस्थान
(b) हिमाचल प्रदेश
(c) पश्चिम बंगाल
(d) मेघालय

Ans ( d )

78. इनमें से कौन सा बाँधों का प्रतिकूल प्रभाव नहीं है?
(a) अंतरराज्यीय जल विवाद
(b) जलाशय का अत्यधिक अवसादन
(c) जनसंख्या का विस्थापन
(d) बाढ़ नियंत्रण
Ans( d )

79. इनमें से किस नदी पर बहुउद्देशीय नदी परियोजना नहीं है?
(a) सतलुज-ब्यास
(b) महानदी
(c) नर्मदा
(d) यमुना
Ans( d )

80. निम्नलिखित में से कौन ताजा पानी का स्रोत है?
(a) वर्षा
(b) भूतल अपवाह
(c) भूजल
(d) उपरोक्त सभी
Ans( c )

81. हीराकुंड बाँध किस नदी पर बनाया गया है?
(a) चेनाब
(b) महानदी
(c) कृष्णा
(d) सतलुज
Ans( b )

82. इनमें से किसने बाँधों को आधुनिक भारत का मंदिर कहा?
(a) राजेन्द्र प्रसाद
(b) जवाहर लाल नेहरू
(c) सरदार पटेल
(d) गाँधी जी
Ans( b )

83. निम्नलिखित में से कौन सा अलवणीय जल का स्रोत है?
(a) वर्षण
(b) सतही जल

(c) भौमजल
(d) उपरोक्त सभी
Ans( d )

84. विश्व में जल के कुल आयतन का कितने प्रतिशत भाग अलवणीय जल है।
(a) 2.5
(b) 3.5
(c) 4.5
(d) 5.5
Ans( a )

85. पहाड़ी और पर्वतीय क्षेत्रों में वर्षा जल संग्रहण के लिए निम्नलिखित में कौन-सी विधि अपनाई जाती है?
(a) जोहड़
(b) जल वाहिकाएँ
(c) खादीप
(d) गुल अथवा कुल
Ans( d )

86.नागार्जुन सागर बाँध किस नदी पर स्थिति है?
(a) चेनाब
(b) महानदी
(c) कृष्णा
(d) सतलुज
Ans( c )

PLEASE SHARE THIS

YOU MIGHT ALSO LIKE

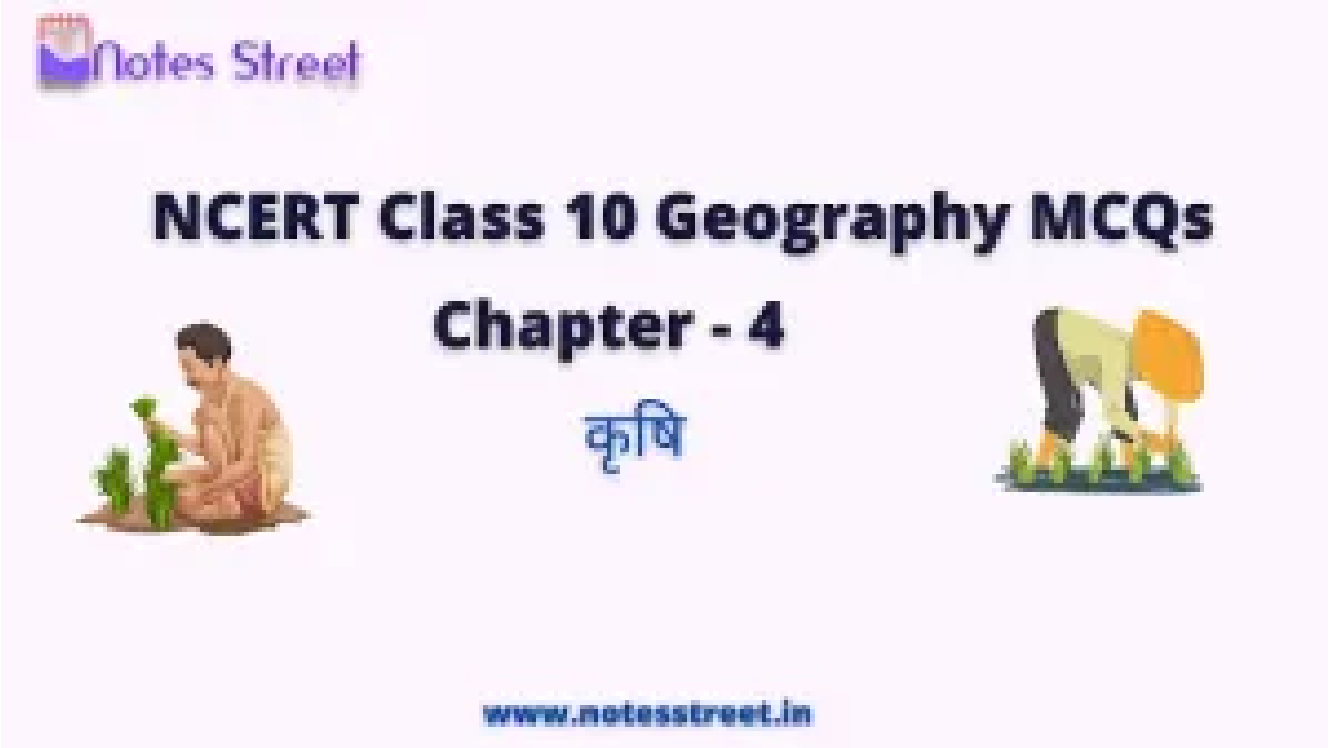


**NCERT Class 10 Geography MCQs Chapter – 4 कृषि**

October 19, 2021

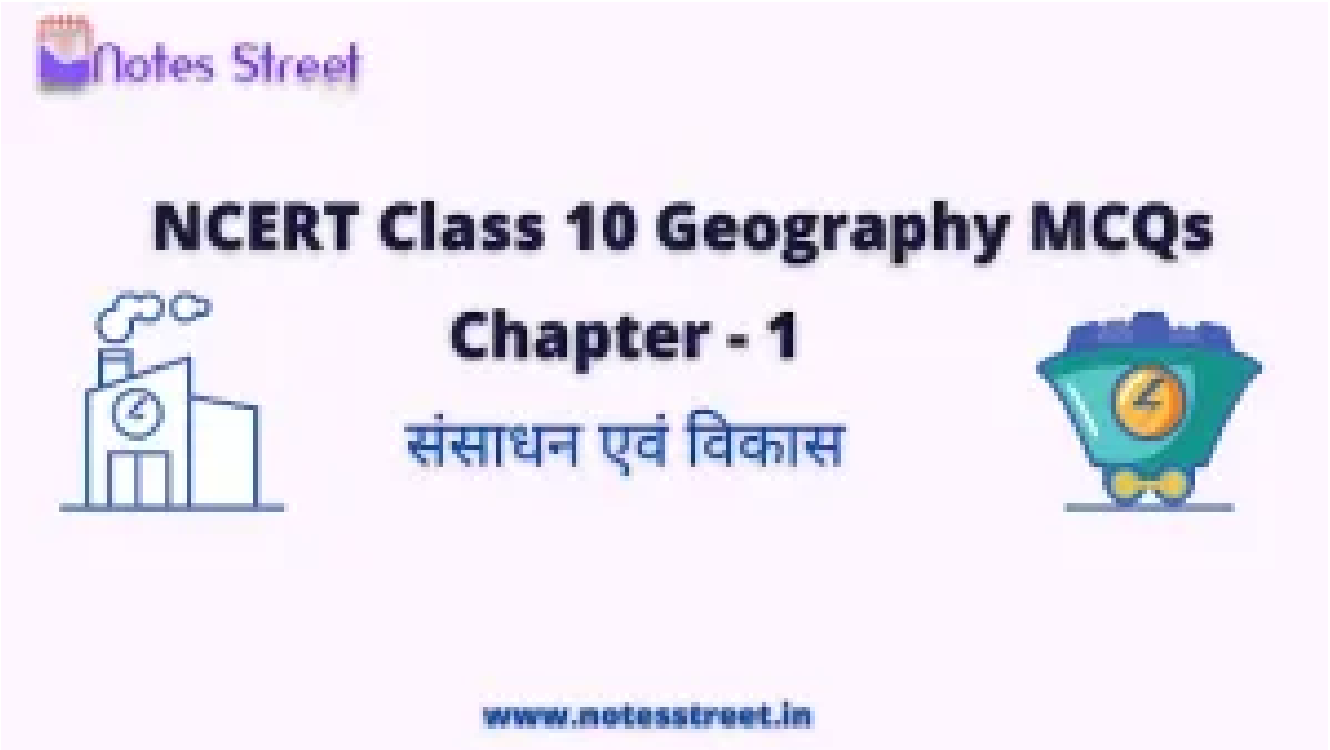


**NCERT Class 10 Geography MCQs Chapter – 1 संसाधन एवं विकास**

October 20, 2021

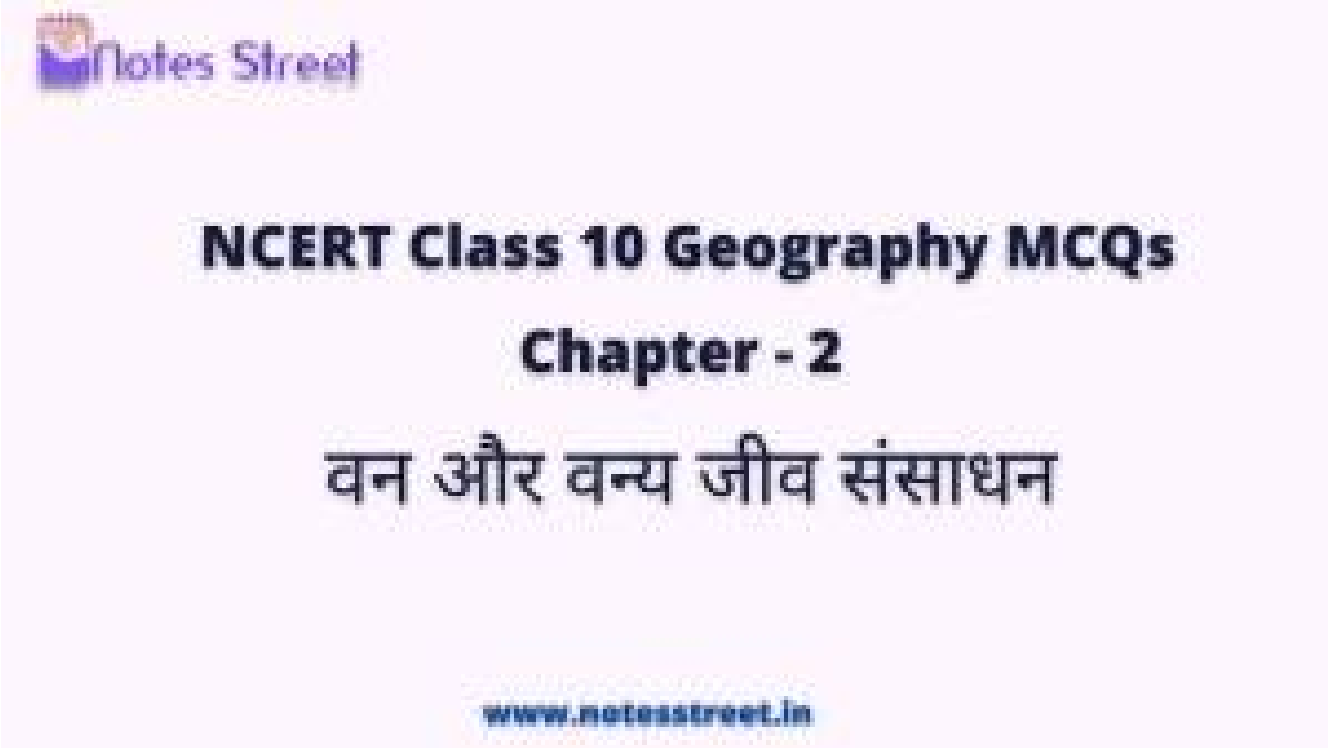


# NCERT Class 10 Geography MCQs Chapter – 2 वन और वन्य जीव संसाधन

April 8, 2022