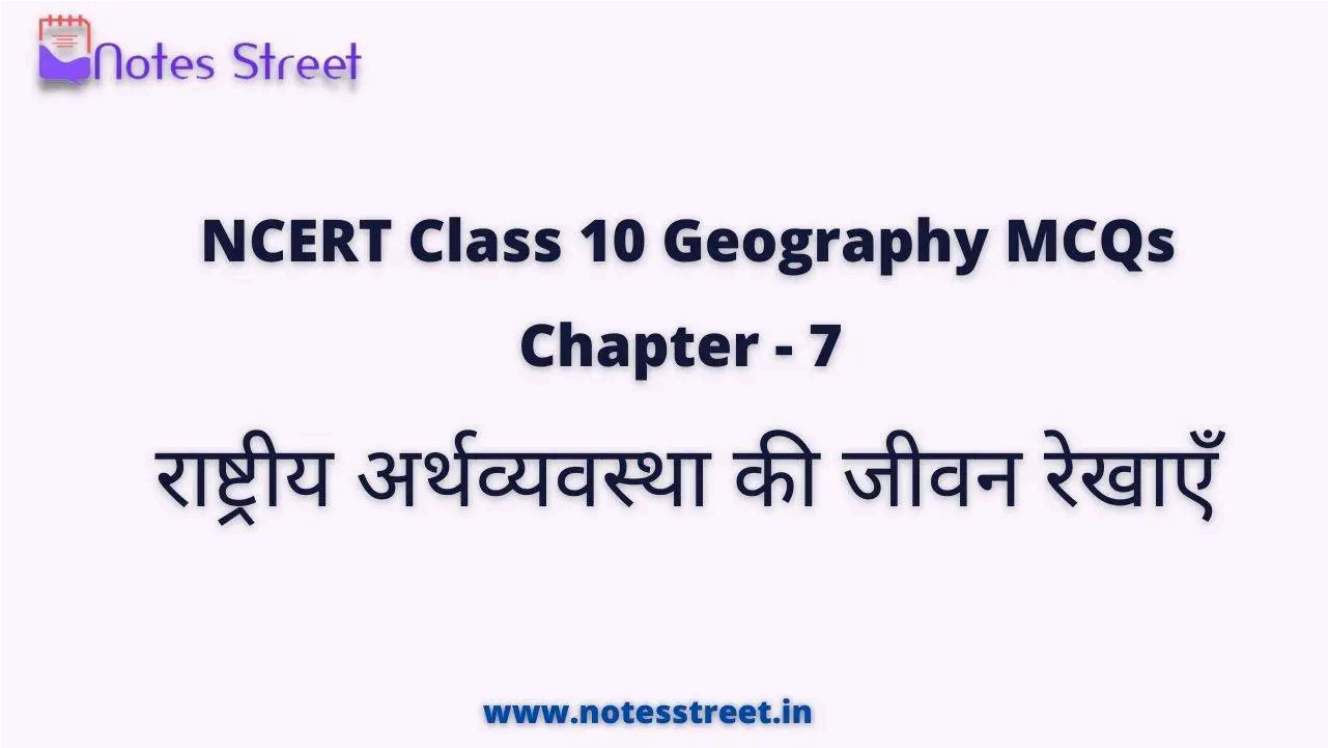

NCERT Class 10 Geography MCQs Chapter – 7 राष्ट्रीय अर्थव्यवस्था की जीवन रेखाएँ

NCERT Class 10 Geography MCQs

Here We are providing **NCERT Class 10 Geography MCQs** Chapter – 7 राष्ट्रीय अर्थव्यवस्था की जीवन रेखाएँ for class 10 students as you know that how NCERT Solution is effective for board exam so that student should practice these NCERT Class 10 Geography MCQs Chapter – 7 राष्ट्रीय अर्थव्यवस्था की जीवन रेखाएँ MCQs Question in Hindi medium and they will get good score in board exams. if you want more notes then **click here**

NCERT Class 10 Geography MCQs Chapter – 7 राष्ट्रीय अर्थव्यवस्था की जीवन रेखाएँ

1. इनमें से किसको भारतीय डाक संचार तंत्र में प्रथम श्रेणी की डाक समझा जाता है।
(a) कार्ड व लिफाफे
(b) रजिस्टर्ड पत्र
(c) पैकेट
(d) रजिस्टर्ड अखबार
उत्तर :- (a)

2. निम्न में से परिवहन के प्रकार कौन-कौन-से है ?
(a) स्थल परिवहन
(b) जल परिवहन
(c) वायु परिवहन
(d) उपरोक्त सभी
उत्तर :- (d)

3. निम्नलिखित में से कौन सा समुद्री पत्तन लौह अयस्क के निर्यात के सन्दर्भ में प्रमुख पत्तन है?
(a) मंगलौर
(b) मार्मागाओ
(c) पारादीप
(d) विशाखापट्नम
उत्तर :- (b)

4. भारत में प्रकाशित समाचार पत्रों की सबसे बड़ी संख्या निम्नलिखित में से किस भाषा में है?
(a) हिंदी
(b) अंग्रेजी
(c) उर्दू
(d) मराठी
उत्तर :- (a)

5. निम्न में से स्थल परिवहन का प्रकार कौन- सा है ?
(a) रेल परिवहन
(b) सड़क परिवहन
(c) a और b दोनों
(d) इनमें से कोई नहीं
उत्तर :- (c)

6. निम्नलिखित में से परिवहन का कौन-सा साधन वाहनांतरण हानियों तथा देरी को घटाता है?
(a) रेल परिवहन
(b) सड़क परिवहन
(c) पाइपलाइन
(d) जल परिवहन
उत्तर :- (c)

7. वर्ष 2014 -2015 के अनुसार भारत में सड़क जाल कितने कि० मी० है ?
(a) 64 .3 लाख की० मी०
(b) 64 लाख की० मी०
(c) 62 लाख की० मी०
(d) 64.3 लाख की० मी०

उत्तर :- (b)

8. भारत में सड़को की सक्षमता के आधार पर कितने वर्गो में बांटा गया है ?
(a) 2
(b) 4
(c) 6
(d) 8
उत्तर :- (c)

9. सबसे लम्बा राष्ट्रीय राजमार्ग कौन-सा है ?
(a) राष्ट्रीय राजमार्ग – 5
(b) राष्ट्रीय राजमार्ग -7
(c) राष्ट्रीय राजमार्ग -1
(d) इनमें से कोई नहीं
उत्तर :- (b)

10. राज्यों की राजधानियों को जिला मुख्यालयो से जोड़ने वाली सड़क क्या कहलाती है ?
(a) राज्य राजमार्ग
(b) महाराजमार्ग
(c) राष्ट्रीय राजमार्ग
(d) जिला मार्ग
उत्तर :- (b)

11. निम्न में से कौन-सा परिवहन साधन भारत में प्रमुख साधन है?
(a) पाइपलाइन
(b) रेल परिवहन
(c) सड़क परिवहन
(d) वायु परिवहन
उत्तर :- (c)

12. दिल्ली और अमृतसर किस राजमार्ग को आपस में जोड़ते है?
(a) राजमार्ग सं० – 3
(b) राजमार्ग सं० – 2
(c) राजमार्ग सं० -1
(d) राजमार्ग संख्या – 7
उत्तर :- (c)

13. ग्रामीण क्षेत्रो तथा गाव को शहर से जोड़ने वाली सड़के किस वर्ग के अंतगर्त आती है ?
(a) जिला मार्ग
(b) राष्ट्रीय मार्ग

(c) राज्य मार्ग
(d) अन्य सड़के
उत्तर :- (d)

14. निम्न में से किस प्रकार की सड़कों को प्रधानमंत्री ग्रामीण सड़क योजना के तहत विशेष प्रोत्साहन मिला?
(a) राष्ट्रीय राजमार्ग
(b) राज्य राजमार्ग
(c) ग्रामीण सड़कें
(d) जिला सड़कें
उत्तर :- (c)

15. सीमा सड़क संगठन कब बनाया गया है ?
(a) 1960
(b) 1961
(c) 1962
(d) 1963
उत्तर :- (a)

16. निम्न में से बारहमासी सड़के कौन-सी है ?
(a) पक्की सड़के
(b) कच्ची सड़के
(c) a और b
(d) इनमें से कोई नहीं
उत्तर :- (c)

17. रेल परिवहन किन – किन कार्यो में सहायक है ?
(a) व्यापार
(b) भ्रमण तथा तीर्थ यात्राए
(c) लम्बी दूरी तक सामान का पारिवहन
(d) उपरोक्त सभी
उत्तर :- (d)

18. भारत में निम्नलिखित में से किस प्रकार की संचार सेवा दुनिया में सबसे बड़ी है?
(a) डाक संचार
(b) टेलीविजन नेटवर्क
(c) इंटरनेट सेवाएं
(d) रेडियो प्रसारण
उत्तर :- (a)

19. मुम्बई से थाने के मध्य चलाई गई रेलगाड़ी ने कितने कि० मी० की दूरी तय की ?
(a) 31 कि० मी०
(b) 32 कि० मी०
(c) 33 कि० मी०
(d) 34 कि० मी०
उत्तर :- (d)

20. निम्न में से कौन से दो दूरस्थ स्थित स्थान पूर्वी-पश्चिमी गलियारे को आपस में जोड़ते है।
(a) मुंबई-नागपुर
(b) सिलचर-पोरबंदर
(c) मुबंई कोलकाता
(d) नागपुर-हैदराबाद
उत्तर :- (b)

21. 31मार्च 2016 तक भारतीय रेल परिवहन की मार्गीय लम्बाई कितनी थी ?
(a) 66687 कि० मी०
(b) 62327 कि० मी०
(c) 51000 कि० मी०
(d) 55402 कि० मी०
उत्तर :- (a)

22. निम्न में कौन सा पत्तन पूर्वी तट पर स्थित है जो अतः स्थलीय तथा अधिकांश गहराई का पत्तन है तथा पूर्ण सुरक्षित है?
(a) चैन्नई
(b) पारादीप
(c) तूतीकोरिन
(d) विशाखापट्नम
उत्तर :- (d)

23. रेल परिवहन के वितरण को प्रभावित करने के कारक कौन-कौन-से हैं ?
(a) भू – आकृतिक कारक
(b) आर्थिक कारक
(c) प्रशासकीय कारक
(d) उपरोक्त सभी
उत्तर :- (d)

24. देश में पाईलाइन परिवहन के कितने प्रमुख साधन है?
(a) 1
(b) 5
(c) 3

(d) 6

उत्तर :- (a)

25. निम्न में से कौन-सा परिवहन साधन तेज व आरामदायक है?

(a) वायु परिवहन

(b) जल परिवहन

(c) सड़क परिवहन

(d) इनमें से कोई नहीं

उत्तर :- (a)

26. राष्ट्रीय जल मार्ग संख्या -1 निम्न में से किन स्थानों के बीच नौका गम्य है?

(a) इलाहाबाद एवं हल्दिया

(b) कोट्टापुरम एवं कोम्मन

(c) कोलकाता से इलाहाबाद

(d) सदिया एवं धुबरी

उत्तर :- (a)

27. देश के प्रमुख संचार साधन कौन-से है ?

(a) दूरदर्शन

(b) रेडियो

(c) प्रेस तथा सीनेमा

(d) उपरोक्त सभी

उत्तर :- (d)

28. अन्तर्राष्ट्रीय व्यापार किसके द्वारा हो सकता है ?

(a) समुद्री मार्ग दवारा

(b) हवाई मार्ग दवारा

(c) स्थलीय मार्ग दवारा

(d) उपरोक्त सभी

उत्तर :- (d)

29. जल परिवहन के कितने प्रकार है ?

(a) 2

(b) 3

(c) 4

(d) 8

उत्तर :- (a)

30. निम्न में से कौन-से दो दूरस्थ स्थित स्थान पूर्वी-पश्चिमी गलियारे से जुड़े हैं?

(a) मुंबई तथा नागपुर

(b) सिलचर तथा पोरबंदर
(c) मुंबई और कोलकाता
(d) नागपुर तथा सिलिगुड़ी
उत्तर :- (b)

31. रेल परिवहन की अपेक्षा सड़क परिवहन की महत्वता के क्या कारण है ?
(a) सड़को की निर्माण लागत बहुत कम है
(b) उबड़-खाबड़ भू-भागों पर भी सड़क बनाई जा सकती है
(c) पहाड़ी क्षेत्रों में भी सड़के बनाई जा सकती है
(d) उपरोक्त सभी
उत्तर :- (d)

32. निम्न में से कौन-सा राज्य हजीरा-विजयपुर-जगदीशपुर पाइपलाइन से नहीं जुड़ा है?
(a) मध्य प्रदेश
(b) महाराष्ट्र
(c) गुजरात
(d) उत्तर प्रदेश
उत्तर :- (b)

33. उत्तर दक्षिण गलियारा किसे जोड़ता है ?
(a) श्रीनगर को कन्याकुमारी से
(b) श्रीनगर
(c) दिल्ली को कन्याकुमारी
(d) इनमें से कोई नहीं
उत्तर :- (a)

34. इनमें से कौन-सा पत्तन पूर्वी तट पर स्थित है जो अंतः स्थानीय तथा अधिकतम गहराई का पत्तन है तथा पूर्ण सुरक्षित है?
(a) चेन्नई
(b) पारादीप
(c) तूतीकोरिन
(d) विशाखापट्टनम
उत्तर :- (d)

35. राष्ट्रीय राजमार्ग – 7 की ल० कितनी है ?
(a) 2465 कि०मी०
(b) 3000 कि०मी०
(c) 2369 कि०मी०
(d) 2567 की०मी०
उत्तर :- (c)

36. निम्न में से कौन-सा शब्द दो या अधिक देशों के व्यापार को दर्शाता है-
(a) आंतरिक व्यापार
(b) अंतरराष्ट्रीय व्यापार
(c) बाहरी व्यापार
(d) स्थानीय व्यापार
उत्तर :- (b)

37. किस क्षेत्र में विशेष प्रावधान के माध्यम से वायु-यात्रा को आम जनता तक पहुचाया गया है?
(a) उत्तरी पूर्वी राज्य
(b) उत्तर राज्य
(c) दक्षिणी राज्य
(d) दक्षिणी पश्चिमी राज्य
उत्तर :- (a)

38. जिला मार्ग की व्यवस्था का उत्तरदायीत्व किसका है ?
(a) राष्ट्रपति
(b) प्रधानमंत्री
(c) जिला परिषद्
(d) मुख्यमंत्री
उत्तर :- (c)

39. भारत की पहली ट्रेन कब और किन दो स्टेशनों के बीच शुरू हुई थी?
(a) कोलकाता से रानीगंज, 1874
(b) मुंबई से ठाणे, 1853
(c) मुंबई से अहमदाबाद, 1854
(d) चेन्नई से अरकोनम, 1856
उत्तर :- (b)

40. भारत में पहली रेलगाड़ी कब चलाई गई ?
(a) 1851
(b) 1852
(c) 1853
(d) 1854
उत्तर :- (c)

41. इन में से कौन उत्तरी भारत का सबसे व्यस्त रेलवे जंक्शन है?
(a) अंबाला
(b) नई दिल्ली
(c) लखन

(d) अमृतसर
उत्तर :- (b)

42. इनमें से नया परिवहन का साधन कौन-सा है ?
(a) पाईपालाइन से
(b) रेलगाड़ी से
(c) ट्रको से
(d) इनमें से कोई नहीं
उत्तर :- (a)

43. इनमें से कौन सी हमारे देश की प्राथमिक सड़क प्रणाली हैं?
(a) राष्ट्रीय राजमार्ग
(b) राज्य राजमार्ग
(c) जिला सड़कें
(d) सीमा सड़कें
उत्तर :- (a)

44. राष्ट्र का आर्थिक बैरोमीटर किसे कहते है?
(a) आंतरिक व्यापार को
(b) राज्यस्तरीय व्यापार को
(c) अन्तर्राष्ट्रीय व्यापार को
(d) क्षेत्रीय व्यापार को
उत्तर :- (c)

45. एसटीडी किसे कहते है?
(a) सब्सक्राइवर ट्रंक डायलिंग
(b) स्पीड टेलीफोन डायलिंग
(c) स्पीड पोस्ट
(d) सब टी डायलिंग
उत्तर :- (a)

46. सबसे सस्ता परिवहन का साधन कौन-सा है?
(a) वायु परिवहन
(b) जल परिवहन
(c) सड़क परिवहन
(d) पाईपलाइन
उत्तर :- (b)

47. उत्तरी रेलवे का मुख्यालय कहाँ स्थित है?
(a) श्रीनगर

(b) भोपाल
(c) दिल्ली
(d) बैंगलोर
उत्तर :- (c)

48. भारतीय व विदेशी फिल्मो को प्रमाणित करने का अधिकार किसे है ?
(a) फिल्मो के निर्देशको को
(b) केन्द्रीय फिल्म प्रमाण बोर्ड
(c) अभिनेता
(d) इनमें से कोई नहीं
उत्तर :- (b)

49.इनमें से कौन सा राष्ट्रीय राजमार्ग देश में सबसे लंबा है?
(a) राष्ट्रीय राजमार्ग संख्या 8
(b) राष्ट्रीय राजमार्ग संख्या 7
(c) राष्ट्रीय राजमार्ग संख्या 4
(d) राष्ट्रीय राजमार्ग संख्या 2
Ans: राष्ट्रीय राजमार्ग संख्या 7
उत्तर :- (b)

50. उत्तर दक्षिण गलिद्वारा किन दो अंतिम सिरों के नगरों को जोड़ता है?
(a) अमृतसर और कन्याकुमारी
(b) श्रीनगर और कन्याकुमारी
(c) श्रीनगर और तिरूवन्तपुरम
(d) श्रीनगर और तुतीकोरिन
उत्तर :- (c)

51. पवन हंस हेलीकाप्टर लिमिटेड किनको अपनी सेवाएं प्रदान कर रहा है?
(a) तेल और प्राकृतिक गैस आयोग
(b) रक्षा मंत्रालय
(c) सेना
(d) पड़ोसी देश
उत्तर :- (a)

52.निम्नलिखित में से कौन परिवहन का सबसे सस्ता साधन है?
(a) रोडवेज
(b) रेलवे
(c) जलमार्ग
(d) एयरवेज
उत्तर :- (c)

53. पक्की सड़के किसके द्वारा निर्मित होती है ?
(a) सीमेंट
(b) कंकरीट
(c) तारकोल
(d) उपरोक्त सभी
उत्तर :- (d)

54. हाल के वर्षों में, भारत इनमें से किस के निर्यात के माध्यम से सबसे ज़्यादा विदेशी मुद्रा अर्जित कर रहा है?
(a) अयस्कों और खनिजों
(b) सूचना प्रौद्योगिकी
(c) कृषि उत्पाद
(d) इलेक्ट्रिकल सामान
उत्तर :- (b)

PLEASE SHARE THIS

YOU MIGHT ALSO LIKE

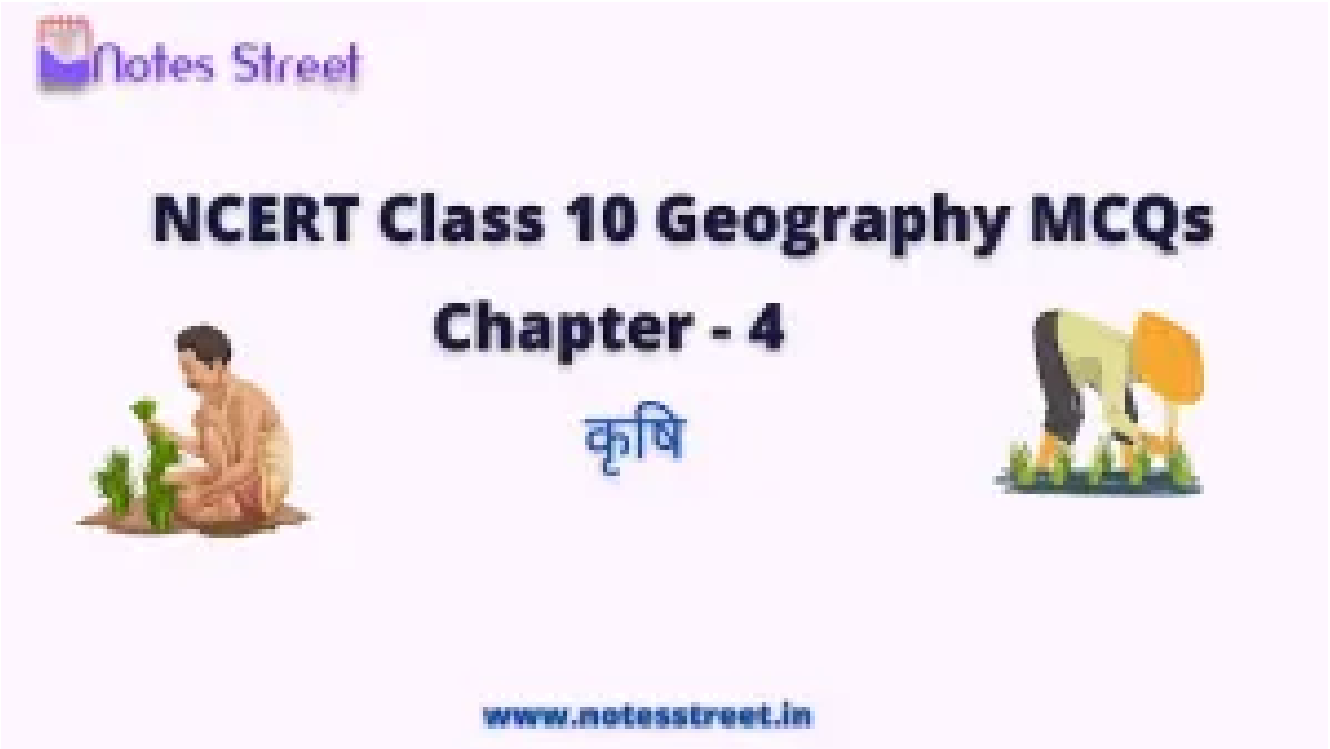

NCERT Class 10 Geography MCQs Chapter – 4 कृषि

October 19, 2021

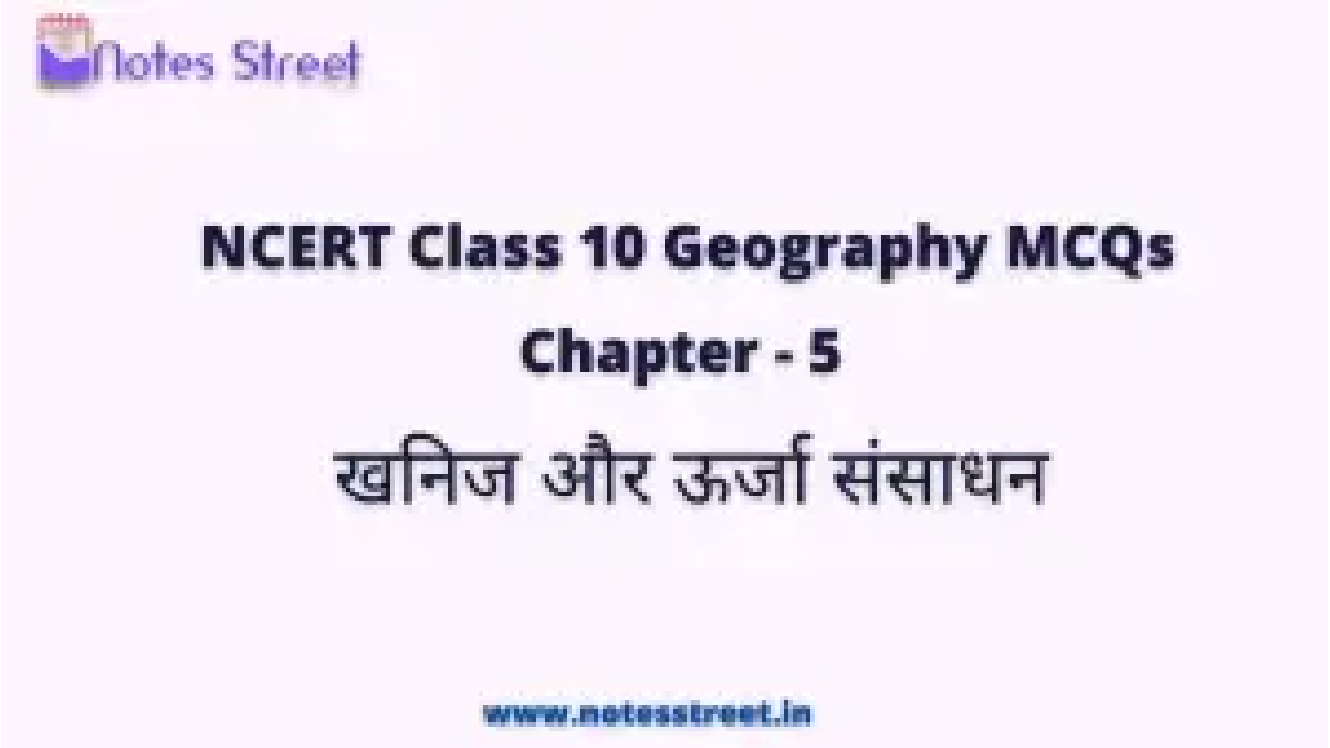

NCERT Class 10 Geography MCQs Chapter – 5 खनिज और ऊर्जा संसाधन

April 8, 2022

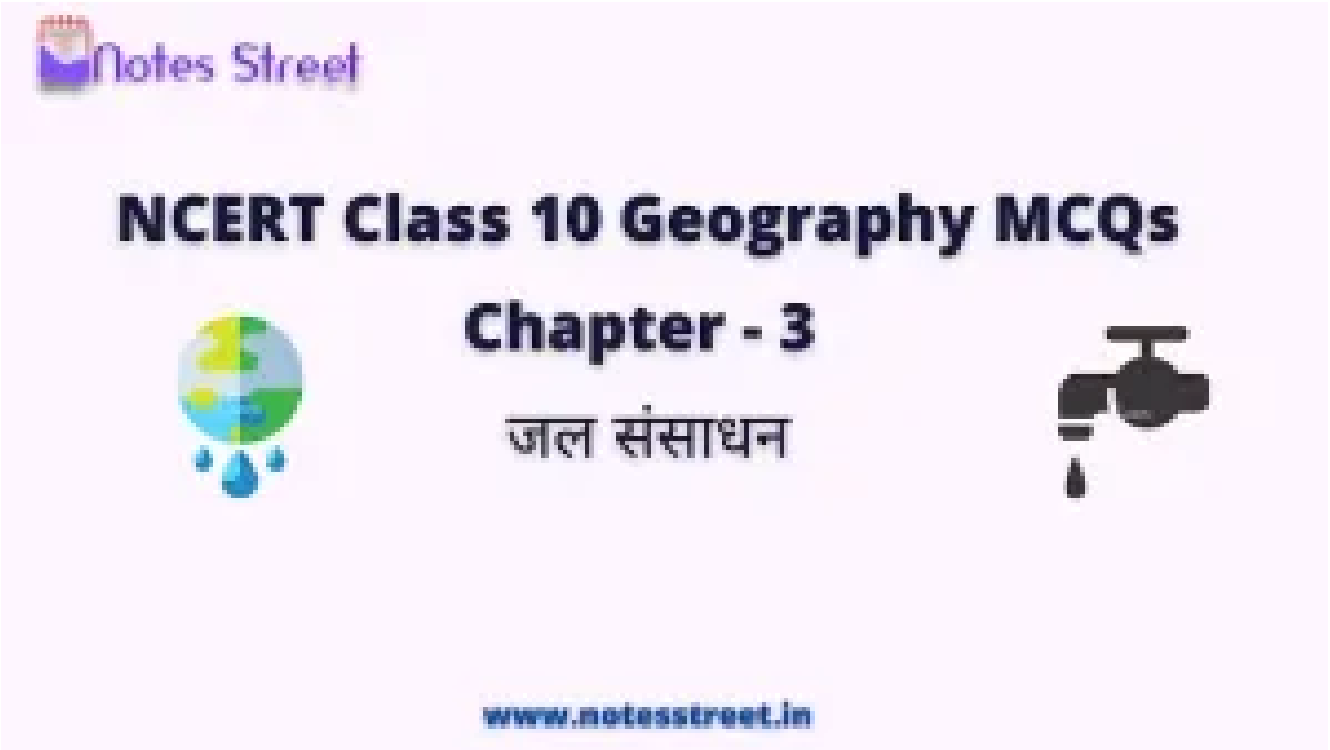

NCERT Class 10 Geography MCQs Chapter – 3 जल संसाधन

October 23, 2021